PLAN MUNICIPAL DE DESARROLLO

Municipio de San Felipe de Jesús
2025-2027

Plan Municipal de Desarrollo
Gobierno Municipal de San Felipe de Jesús, 2025-2027

La utilización o reproducción, total o parcial, de textos, gráficos, fotografías, o contenidos con fines no lucrativos sólo está permitida si se hace constar la procedencia del material y el autor de estas.

Gobierno Municipal

SAN FELIPE DE JESÚS

2025-2027

C. JESÚS ALBERTO BALLESTEROS QUIROGA
Presidente Municipal

C. CRUZ ELENA ALVARADO VÁSQUEZ
Síndica Procuradora

C. JAVIER OLIVAS LÓPEZ
Regidor

C. MARÍA DE LOS ÁNGELES PERALTA ROMERO
Regidora

C. MARIO BALLESTEROS QUIROGA
Regidor

C. JESÚS ARMANDO MALDONADO FIGUEROA
Regidora

C. MARÍA CAROLINA QUIJADA COPETILLO
Regidora

ÍNDICE DE CONTENIDO

MENSAJE DEL PRESIDENTE MUNICIPAL 6
I. INTRODUCCIÓN 7
Fundamentación Jurídica 7
Alineación al Plan Nacional de Desarrollo 9
Alineación al Plan Estatal de Desarrollo 2022-2027 10
II. METODOLOGÍA 11
III. PRINCIPIOS RECTORES 13
Misión 13
Visión 13
Valores institucionales 13
IV. DIAGNÓSTICO-PRONÓSTICO INTEGRADO 14
Rasgos históricos y medio físico natural 14
Fisiografía 15
Hidrografía 15
Geología 15
Edafología 16
Uso de suelo y vegetación 16
Aptitud territorial 16
Clima 16
Calidad del agua 16
Flora 17
Fauna 17
Características sociodemográficas 17
Hogares, vivienda y disponibilidad de servicios públicos, bienes y tecnología de información y comunicación 21
Situación económica 21
Situación del equipamiento 23
Educación 23
Salud 23
Cultura, recreación y deporte 23
Servicios públicos 23
Servicio de agua 23

Recolección de basura 24
Alumbrado público 25
Caminos y pavimentación 26
Espacio público 26
Seguridad Pública 28
Áreas de oportunidad según sondeo 28
Fortalezas de la administración según sondeo 29
FODA Social 30
FODA Económico 31
V. EJE ESTRATÉGICO 1: GOBIERNO EFICIENTE Y HONESTO 32
VI. EJE ESTRATÉGICO 2: BIENESTAR SOCIAL 35
VII. EJE ESTRATÉGICO 3: LA IGUALDAD EFECTIVA DE LOS DERECHOS Y EL ACCESO A SERVICIOS PÚBLICOS DE CALIDAD 37
VIII. EJE ESTRATÉGICO 4: DESARROLLO ECONÓMICO, SEGURIDAD Y SUSTENTABILIDAD 39
IX. COMPROMISOS ESPECÍFICOS DEL MUNICIPIO DE SAN FELIPE DE JESÚS CON BASE EN EL PLAN ESTATAL DE DESARROLLO 2022-2026 40
X. COMPROMISOS GENERALES DE CAMPAÑA CON COBERTURA ESTATAL CON BASE EN EL PLAN ESTATAL DE DESARROLLO 2022-2026 41
XI. EVALUACIÓN Y SEGUIMIENTO DEL PLAN MUNICIPAL DE DESARROLLO 47
Enfoque de la Evaluación 47
XII. MATRICES DE INDICADORES DE RESULTADOS 50
XIII. BIBLIOGRAFÍA 64

MENSAJE DEL PRESIDENTE MUNICIPAL

San Felipe de Jesús sin duda ha presentado avances importantes en los últimos tres años, sin embargo, estamos conscientes que enfrentamos retos mayores, ya que poder brindar servicios públicos de calidad en el municipio es nuestro objetivo principal, así mismo mejorar la imagen urbana, mantener la seguridad y detonar fuentes de desarrollo económico a través del autoempleo y del colectivo.

Este Plan nos marca la continuidad de un trabajo ya avanzado en la administración anterior, donde no solo vemos por el futuro inmediato, sino dejamos cimientos fuertes y sólidos a largo plazo; es por ello que se proponen un conjunto de estrategias innovadoras para enfrentar de manera distinta los problemas que nos aquejan, pero reconocemos que la meta no se logrará solamente por la voluntad y esfuerzo de las autoridades municipales, sino con la participación de la ciudadanía activa, que alimente y engrose las decisiones públicas y evalúe sus efectos, que se haga parte de la construcción de la prosperidad y la sustentabilidad, que sea efectiva la exigencia con sus aportaciones y participaciones, pues solo así, juntos vamos a lograr que San Felipe de Jesús, sea un mejor lugar para vivir.

Señalo que el presente plan es un instrumento que nos marca rumbo, pero también, coadyuva a construir un gobierno austero, honesto, eficaz y de políticas públicas que impactan directamente en la vida de nuestra población; sin duda, es un documento abierto, sujeto a la mejora continua del quehacer gubernamental y la mejora de la dinámica social demandada.

Por último, las necesidades que se reflejaron en las mesas de trabajo, sesiones de Ayuntamiento abierto y demás herramientas de participación ciudadana utilizada para construir el presente plan; nos dieron el diagnóstico correcto de lo que se ha venido haciendo bien y de lo que hay que corregir y continuar, es por ello que, estamos seguros que San Felipe de Jesús, seguirá teniendo bienestar, desarrollo y seguirá siendo un mejor lugar para vivir.

Afectuosamente

C. JESÚS ALBERTO BALLESTEROS QUIROGA
PRESIDENTE MUNICIPAL

I. INTRODUCCIÓN

El Plan Municipal de Desarrollo 2024-2027 representa la continuidad del proyecto emprendido en el periodo 2021-2024. Bajo este instrumento se mantienen y redireccionan los objetivos del actuar municipal con una visión de futuro y largo plazo.

Su conformación parte del reconocimiento de las problemáticas que aquejan al municipio, anteponiendo siempre el sentir de sus pobladores. La construcción del plan retoma una rigurosidad relacionada a la participación ciudadana a partir de encuestas que posibilitan identificar las políticas, planes y proyectos exitosos y encaminados hacia el bienestar de la población, así como aquellos aspectos que merecen mayor atención para su rencauzamiento

La estructura del documento se compone de 12 apartados: Los primeros tres se enfocan en la congruencia del plan con los marcos jurídicos vigentes, su alineación con los planes estatal y nacional; la metodología aplicada; así como los principios rectores en los que se expresa la misión y visión que la administración municipal seguirá.

El siguiente apartado es el Diagnóstico, en el cual se aprecia la situación que vive el municipio. Sus primeras líneas parten de un análisis cuantitativo y cualitativo basado en fuentes oficiales como el INEGI, CONAPO y CONEVAL; mientras que las líneas siguientes se respaldan por un análisis descriptivo elaborado por la información que las encuestas hechas a los habitantes del municipio arrojaron. Por último, este apartado concluye con un análisis de Fortalezas, Oportunidades, Debilidades y Amenazas, dividido para una mayor facilidad de lectura, en uno social y otro económico.

Posterior al reconocimiento de la situación, se construyen las propuestas. En este sentido, los siguientes siete apartados representan el corazón del programa: los objetivos, las estrategias, las líneas de acción y, como complemento, un listado de compromisos inscritos en el Plan Estatal de Desarrollo.

Por último, el Plan presenta los mecanismos que deberán ser utilizados para su evaluación, así como una serie de indicadores que serán utilizados para la medición del desempeño de los objetivos, estrategias y líneas de acción propuestas.

Fundamentación Jurídica

El sustento legal y normativo para la formulación del Plan Municipal de Desarrollo está determinado por distintos ordenamientos jurídicos de escala federal, estatal y municipal. Se parte del orden jurídico máximo, la **Constitución Política de los Estados Unidos Mexicanos** (1917), que establece en su artículo 25 que "…Corresponde al Estado la rectoría del desarrollo nacional para garantizar que éste sea integral y sustentable, que fortalezca la Soberanía de la Nación y su régimen democrático y que, mediante la competitividad, el fomento al crecimiento económico y el empleo y una más justa distribución del ingreso y la riqueza, permita el pleno ejercicio de la libertar y la dignidad de los individuos, grupos y clases sociales, cuya seguridad protege esta Constitución…"; asimismo, el artículo 26, le confiere al estado la organización de un sistema para la planeación democrática para el desarrollo nacional, establecer procedimientos de participación e incorporar

diversas demandas de la sociedad al plan y los programas de desarrollo. Sobre esta línea, se desarrolla el Plan Nacional de Desarrollo como uno de los principales referentes para la estructuración de los planes municipales y su alineación con los distintos órdenes de gobierno.

Por su parte, en el artículo 115, la Constitución establece la base de la división territorial, de la organización política y administrativa del estado consagrada en el municipio libre. En la fracción V inciso "a" del mismo artículo se menciona que los municipios están facultados para formular, aprobar y administrar la zonificación de planes de desarrollo urbano municipal, en los términos de las leyes federales y estatales respectivas.

En cuanto al enfoque de desarrollo sostenible, que busca "satisfacer las necesidades del presente sin comprometer la capacidad de generaciones futuras de satisfacer sus propias necesidades" (Informe Brundtland, 1987), el Plan Municipal de Desarrollo contempla la **Agenda 2030** aprobada en 2015 por la Organización de las Naciones Unidas (ONU), con la estructuración de 17 Objetivos de Desarrollo Sostenible (ODS) (ONU México, 2015), los cuales son alineados con los ejes estratégicos del presente plan: **Eje estratégico 1**, gobierno eficiente y honesto; **Eje estratégico 2**, bienestar social; **Eje estratégico 3**, la igualdad efectiva de los derechos y el acceso a servicios públicos de calidad; y, **Eje estratégico 4**, desarrollo económico, seguridad y sustentabilidad.

Tabla 1. Alineación a la Agenda 2030 de Desarrollo Sostenible

Objetivos de Desarrollo Sostenible	Plan Municipal de Desarrollo 2024-2027
1. Fin de la pobreza	Eje estratégico 2
2. Hambre cero	Eje estratégico 2
3. Salud y bienestar	Eje estratégico 2
4. Educación de calidad	Eje estratégico 2
5. Igualdad de género	Todos los ejes estratégicos
6. Agua limpia y saneamiento	Eje estratégico 3
7. Energía asequible y no contaminante	Ejes estratégicos 2 y 4
8. Trabajo decente y crecimiento económico	Ejes estratégicos 2 y 4
9. Industria, innovación e infraestructura	Ejes estratégicos 2 y 4
10. Reducción de desigualdades	Ejes estratégicos 2, 3 y 4
11. Ciudades y comunidades sostenibles	Ejes estratégicos 1 y 4
12. Producción y consumo responsables	Ejes estratégicos 1 y 4
13. Acción por el clima	Eje estratégico 1
14. Vida submarina	No aplica
15. Vida de ecosistemas terrestres	Ejes estratégicos 3 y 4
16. Paz, justicia e instituciones sólidas	Ejes estratégicos 1 y 3
17. Alianzas para lograr objetivos	Eje estratégico 1

Fuente: Elaboración propia con información tomada de la Agenda 2030 de Desarrollo Sostenible (ONU, 2014).

En cuanto al resto de los ordenamientos jurídicos a los que se sujeta el presente documento, se exhiben enlistados a continuación:

- Ley Nacional de Planeación
- Ley Orgánica de la Administración Pública Federal
- Constitución Política del Estado Libre y Soberano de Sonora

- Ley de Planeación de Sonora (289)
- Ley General de Equilibrio Ecológico y Protección al Ambiente
- Ley de Equilibrio Ecológico y Protección al Ambiente para el Estado de Sonora
- Ley de Desarrollo Urbano del Estado de Sonora
- Ley de Gobierno y Administración Municipal
- Reglamento del Comité de Planeación Municipal

Alineación al Plan Nacional de Desarrollo

El presente Plan Municipal de Desarrollo en atención al artículo 1 fracción II, 2 fracción I y 10 de la Ley de Planeación del Estado de Sonora se alinea con el Plan Nacional de Desarrollo (PND) 2025-2030. Al respecto, se retoma la propuesta de la Administración Federal entrante, aún en proceso de elaboración, pero con los ejes generales definidos al momento de construir este documento.

Se prevé una continuidad sobre lo que se llamó modelo posneoliberal en el PND 2018-2024, viable para el ordenamiento político y el desarrollo económico y social planteado sobre una nueva ética política y una democracia cada vez más participativa.

Entre los principales elementos que conforman este cambio de paradigma se encuentran: la lucha contra la corrupción, la separación del poder político del económico, la redistribución del ingreso por la vía de apoyos directos a grupos necesitados, así como líneas que potencien el desarrollo como la educación y la salud, la seguridad y la paz, además del fin del neoliberalismo con el establecimiento de un modelo económico que da prioridad al mercado interno y la soberanía energética.

Los ejes transversales que se presentan en el nuevo PND son la igualdad sustantiva y derechos de las mujeres, la innovación pública para el desarrollo tecnológico nacional, así como los derechos de las comunidades indígenas y afromexicanas.

Tabla 2. Alineación al Plan Nacional de Desarrollo

Plan Nacional de Desarrollo 2025-2030	Plan Municipal de Desarrollo 2024-2027	Punto de encuentro:
Gobernanza con justicia y participación ciudadana	Gobierno eficiente y honesto	Abordan la erradicación de la corrupción, separar el poder político del económico, así como líneas para reactivar la procuración de justicia, la garantía de empleo, educación, salud y bienestar bajo el respeto de los derechos humanos. Asimismo, se contemplan finanzas sanas a partir de un uso responsable de los recursos.
Desarrollo con bienestar y humanismo	Bienestar social y la igualdad efectiva de los derechos y el acceso a servicios públicos de calidad	Bajo ambos ejes se busca garantizar que todas las personas puedan cubrir sus necesidades básicas, especialmente aquellas en situación de pobreza, desigualdad o marginación.
Economía moral y trabajo / Desarrollo sustentable	Desarrollo económico, seguridad y sustentabilidad	Establece los aspectos a impulsar para lograr un crecimiento económico a partir de la inversión privada, la construcción de infraestructura, proyectos turísticos, apoyos a los productores, siempre bajo medidas que aborden la sustentablidad, así como condiciones laborales diganas que promuevan el bienestar de los trabajadores.

Fuente: Elaboración propia con información tomada del PND 2018-2024 (2019).

Alineación al Plan Estatal de Desarrollo 2022-2027

Con fundamento en el artículo 45 de la Ley de Planeación del Estado de Sonora, se alinea el presente Plan Municipal de Desarrollo con los ejes que promueve el Plan Estatal de Desarrollo 2022-2027.

Tabla 3. Alineación al Plan Estatal de Desarrollo

Plan Estatal de Desarrollo 2022-2027	Plan Municipal de Desarrollo 2024-2027	Punto de encuentro:
Un gobierno para todas y todos	Gobierno eficiente y honesto	Abordan el impulso al fortalecimiento municipal, así como el buen gobierno para la regeneración democrática.
El presupuesto social más grande de la historia	Bienestar social	Incluyen una política común social y solidaria para el bienestar, así como la búsqueda de salud universal.
La igualdad efectiva de los derechos	La igualdad efectiva de los derechos y el acceso a servicios públicos de calidad	Integran políticas que alcancen una verdadera equidad de género, así como la igualdad de los derechos. En el caso municipal, se promueve el acceso a servicios públicos de todos sus pobladores, sin distinción.
Una coordinación histórica entre desarrollo y seguridad	Desarrollo económico, seguridad y sustentabilidad	Desde un enfoque donde la seguridad pública y el desarrollo económico se vinculan, se integran políticas para la reactivación del crecimiento económico con finanzas sanas, construcción de infraestructura y un enfoque de desarrollo económico inclusivo y sustentable.

Fuente: Elaboración propia según indicaciones de la Coordinación de Planeación y Comisiones del Consejo Consultivo para el Plan Estatal de Desarrollo 2021-2027.

II. METODOLOGÍA

A partir del 2008, las administraciones públicas de los tres órdenes de gobierno han realizado un proceso de cambio y modernización mediante la adopción del modelo de la Gestión por Resultados (GpR) o en su traducción original llamada Planeación de Proyectos Orientada a Objetivos. A raíz de esto, se integró la Metodología de Marco Lógico (MML) definida como el conjunto de herramientas para presentar de forma sistemática y lógica los objetivos de un plan y las relaciones de causalidad con los problemas que se busca atender (PNUD México, 2019).

La Gestión para Resultados (GpR), orienta a las instituciones al cumplimiento de resultados a partir del nuevo paradigma de gestión pública. Su principal misión es administrar e implementar los recursos públicos con enfoque a los resultados deseados y utilizar la información para mejorar la toma de decisiones. Entre los pilares de la GpR, tenemos por un lado las actividades de seguimiento y evaluación, y por otro las actividades de auditoría.

De esta manera, podemos aseverar que en el marco de la GpR, las funciones de seguimiento, evaluación y auditoría son complementarias porque persiguen fines comunes, pero con diferencias que es menester resaltar. En la siguiente figura se resumen las principales características de estos tres instrumentos de valoración que promueven una gestión pública orientada a resultados.

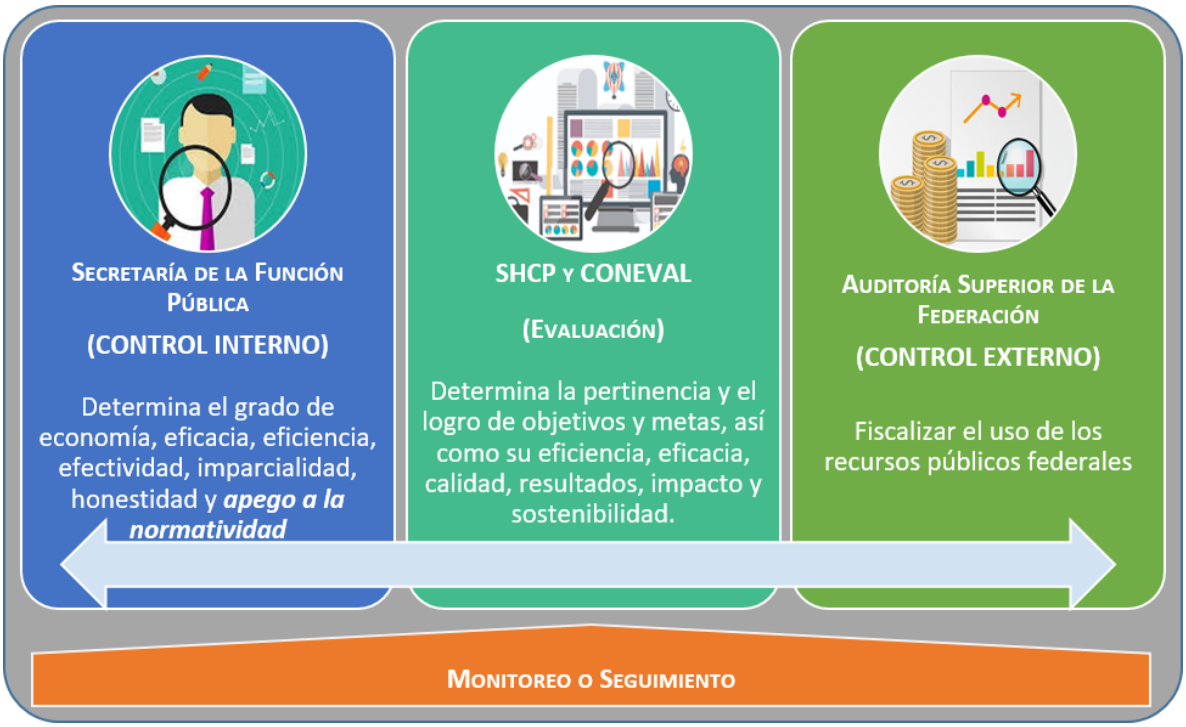

Fuente: Secretaría de Hacienda y Crédito Público (2019).

Cabe señalar que el seguimiento es un requisito previo indispensable para la aplicación de los instrumentos de evaluación o auditoría, ya que permite la generación sistemática de información confiable sobre la asignación y el ejercicio de los recursos públicos destinados a la gestión gubernamental, haciendo posible su valoración en diferentes ámbitos, según las necesidades de los tomadores de decisiones (gestión, desempeño o gasto). Por esta razón es indispensable que el

seguimiento y la evaluación no se vean como procesos independientes sino como momentos complementarios fuertemente vinculados por los indicadores de desempeño.

A grandes rasgos, la MML articula una serie de técnicas secuenciales orientadas a construir diagnósticos, diseñar políticas, planes, programas y proyectos alineados a objetivos de desarrollo más amplios, en este caso alineados a los Objetivos de Desarrollo Sostenible de la Agenda 2030 y a los ejes enunciados en el Plan Nacional de Desarrollo. Su estructura se compone por las siguientes etapas:

1. Definición del problema
2. Análisis de involucrados
3. Árbol de objetivos
4. Selección de alternativas: creación de la Matriz de Indicadores de Resultados (MIR)

Durante este proceso, la participación ciudadana juega un papel fundamental para la definición de los problemas y la consecuente formulación y consulta de las alternativas de solución.

Para el desarrollo de este documento, se inició con la consulta de fuentes oficiales y las líneas de administraciones municipales anteriores para conocer el estado actual del municipio.

Subsecuentemente, al contar con una aproximación cuantitativa de la problemática municipal, se llevó a cabo una encuesta para corroborar la información obtenida y, en mayor medida, identificar aquellas líneas de acción que deben ser mantenidas, intensificadas o reencauzadas.

Bajo este proceso, se pretende garantizar un rumbo claro hacia la definición de soluciones certeras y tangibles. Por ello, se refrenda el Comité de Planeación Municipal (COPLAM) del periodo 2021-2024, cuyos participantes integraron las mesas de trabajo para reconocer la problemática que aqueja al municipio desde el periodo administrativo anterior. A partir de este encuentro y con base en la información recabada previamente, se creó un árbol de problemas del cual se desprendieron los principales aspectos a actualizar.

Por último, se desarrollaron las alternativas de trabajo o líneas de acción sobre las que el PMD propone trabajar.

III. PRINCIPIOS RECTORES

Misión

Hacer de San Felipe de Jesús un municipio con un gobierno abierto, participativo y unido donde las decisiones, acciones, obras y metas tengan por objetivo el beneficio ciudadano en todo momento y elevar su calidad de vida. Con la firme misión de ser un gobierno de cambio comprometido con el desarrollo, brindando un trato justo y de igualdad social. Donde nuestro municipio sea innovador, competitivo, ordenado y sustentable.

Un gobierno cercano e incluyente promoviendo la participación de los ciudadanos, en todos los sectores sociales a través de una comunicación permanente y transparente en el manejo de los recursos humanos, materiales, financieros y tecnológicos, que involucre a los Sanfelipenses a fin de que juntos, construyamos el San Felipe de Jesús que todos queremos y tener de Calidad a través de una gestión Municipal sensible a las necesidades de la ciudadanía, bajo un marco de legalidad y confianza para que sea un mejor municipio para vivir.

Visión

Nuestra visión es que, a través de un trabajo participativo, abierto a escuchar y encontrar de la mano de la ciudadanía las mejores alternativas, logremos al término de esta administración un San Felipe de Jesús de vanguardia, con mecanismos, programas y obras que impacten positivamente en la vida de sus habitantes y en la economía de la región de manera permanente. Dejando los cimientos de un proyecto a largo plazo para no detener la evolución y progreso de nuestro municipio.

Valores institucionales

Los valores institucionales forman parte de la convicción compartida dentro de la Administración Municipal. Su mención es pertinente para el reconocimiento moral y ético con el que se actúa, estos valores en atención de los estipulados en el Código de ética y conducta de los servidores públicos del H. Ayuntamiento de San Felipe de Jesús, Sonora, publicado en el Boletín Oficial del Gobierno del Estado de Sonora en el tomo CCIII número 28, sección I, de fecha lunes 8 de abril de 2019.

- Honestidad
- Compromiso
- Responsabilidad
- Respeto
- Eficiencia
- Solidaridad
- Imparcialidad
- Transparencia
- Honradez
- Trabajo en equipo

IV. DIAGNÓSTICO-PRONÓSTICO INTEGRADO

Rasgos históricos y medio físico natural

San Felipe de Jesús fue fundado en el año 1657, cuando el capitán Juan Munguía Villela denunció los terrenos para el establecimiento de una hacienda dedicada a la extracción de minerales. A diferencia de la mayoría de los asentamientos del río Sonora, su fundación no responde a los centros de población establecidos por el jesuita Bartolomé Castaño, por lo que fue considerada una hacienda de beneficio más que una misión.

En 1862, la participación de sus pobladores en la intervención francesa le concedió el grado de municipio a partir de un decreto elaborado en la presidencia de Benito Juárez. Sin embargo, años más tarde fue incorporado al distrito de Arizpe (1906), posteriormente, perteneció al de Ures (1930), un año más tarde al de Banámichi (1931) y finalmente rehabilitado como municipio el 10 de junio del año 1932.

San Felipe de Jesús es el municipio de menor extensión territorial del estado de Sonora con 151.3 kilómetros cuadrados que representan el 0.8% de la superficie estatal. Su ubicación es al centro de la entidad, en el paralelo 29° 51’ de latitud norte y a los 110° 14’ de longitud al oeste del meridiano de Greenwich. La altitud del municipio ronda entre los 500 y 1,900 metros de altura sobre el nivel del mar; su cabecera municipal y principal centro de población, San Felipe de Jesús, se encuentra a 853 metros sobre el nivel del mar.

El municipio colinda al norte y oriente con el municipio de Huépac, al poniente con Opodepe y al sur con Aconchi y Rayón.

En cuanto a su ubicación respecto a centros urbanos de mayor tamaño, San Felipe de Jesús se encuentra a 233 kilómetros lineales al sureste de la ciudad fronteriza de Nogales y a 159 kilómetros de la ciudad de Hermosillo, capital del estado. El acceso al pueblo desde esta última ciudad se realiza a través de la carretera federal 14 (Hermosillo-Moctezuma) con una desviación para tomar la carretera estatal 89 (Mazocahui-Cananea). Cabe mencionar que San Felipe de Jesús es la única cabecera municipal localizada fuera del paso de la carretera estatal, lo que supone una desviación que implica cruzar el río Sonora por medio de un vado vehicular o un puente peatonal.

Figura 1. Localización del municipio de San Felipe de Jesús

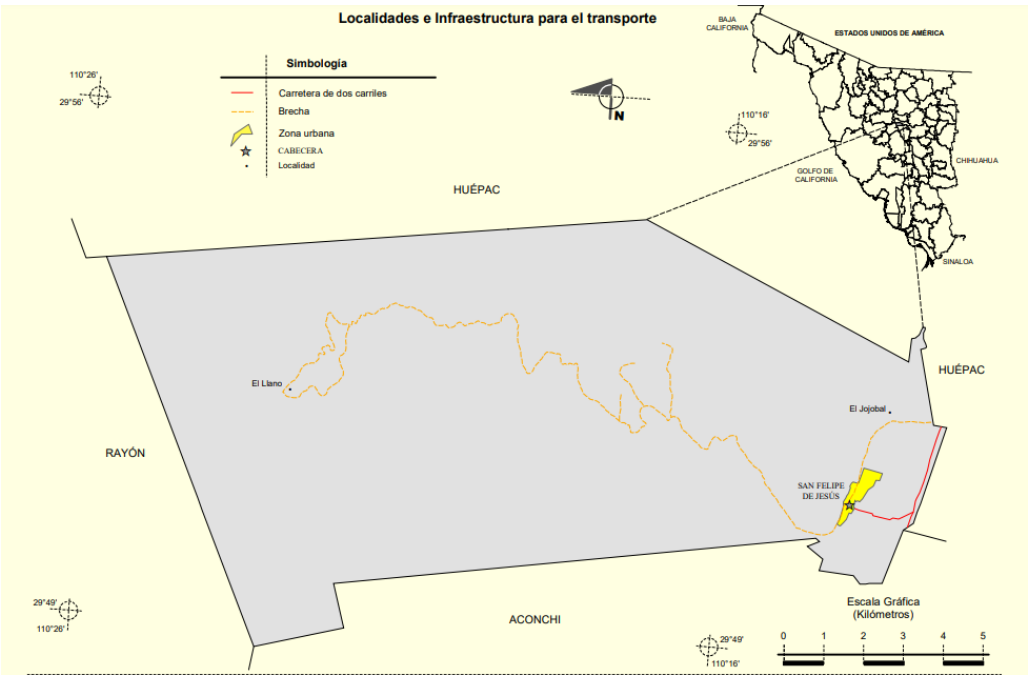

Fuente: Tomado del Prontuario de información geográfica municipal de los Estados Unidos Mexicanos, Municipio de San Felipe de Jesús, Sonora. INEGI, 2009.

Fisiografía

De manera generalizada, el municipio presenta tres formas de relieve: la sierra alta como forma mayoritaria, con el 83.5% de la extensión municipal; de lomeríos típicos con el 11.9% del territorio; y un valle intermontañoso que representa el 4.6% de la superficie.

Hidrografía

El territorio de San Felipe de Jesús pertenece en su mayor parte a la cuenca del río Sonora (97.2%); mientras que una pequeña porción de su territorio occidental forma parte de la cuenca del río San Miguel (2.8%). El río Sonora es la única corriente de agua perenne, subterránea la mayor parte del año; mientras que como afluentes intermitentes de éste se encuentran los arroyos del Agua Caliente, Cajón Hondo, El Lavadero, El Potrero y el Huerobabi (INEGI, 2009).

Según información del INAFED (2021), dentro de su sistema de abastecimiento hídrico, el municipio cuenta con 4 pozos equipados y dos tajos que apoyan a la agricultura, además de 5 represas y un pozo de abrevadero dentro del ejido.

Geología

En términos geológicos, la superficie del municipio se distribuye en 3 periodos: 49.1% con formaciones del periodo cretácico, 7.2% con formaciones del periodo cuaternario y 1.8% como no definido.

En cuanto al tipo de rocas que sobresalen, 49% es roca ígnea intrusiva o granito, 22.3% es roca ígnea extrusiva presente en riolita-toba ácida, otra parte se compone de rocas sedimentaria (19.5% de conglomerado y 1.84% de conglomerado) y, por último, 7.21% es de aluvial.

Edafología

Existen dos tipos de suelo dominante: el Leptosol con 49.7% de la superficie y el Regosol con 43.5%. El suelo restante se compone de Fluvisol (6.5%) y Phaeozem (0.04%).

Uso de suelo y vegetación

La zona urbana, representada en su gran mayoría por la cabecera municipal, ocupa el 0.33% del territorio; mientras que 5.33% es considerado para uso agrícola; 55.12% como selva seca; 37.4% como bosque; 0.32% como pastizal; y 1.45% sin definir (INEGI, 2009).

Aptitud territorial

Como uso potencial de la tierra, el Prontuario de Información Geográfica Municipal (2009) indica que 98.7% de la tierra no es apta para la agricultura y sólo 1.3% lo es para agricultura mecanizada continua. En cuanto al uso pecuario, el mismo documento señala que 53.1% del territorio no es apto para uso pecuario, 45.6% es apto para el aprovechamiento de la vegetación natural diferente del pastizal y 1.25% es apto para el desarrollo de praderas cultivadas actualmente con uso agrícola.

Clima

El municipio de San Felipe de Jesús cuenta con un clima seco semiseco templado Bsohw (x) (e), con una temperatura media máxima mensual de 25.3 °C en los meses de julio y agosto y una mínima mensual de 8.3°C. en los meses de diciembre y enero.

El periodo de lluvias se presenta en verano en los meses de julio y agosto contándose con una precipitación media anual de 468.8 milímetros. El riesgo de heladas es frecuente por su proximidad a la sierra del río Sonora, sobre todo entre los meses de noviembre a marzo (INAFED, 2021).

Figura 2. Climograma (1981-2010): Estación Huépac, Sonora (más cercana a San Felipe de Jesús)

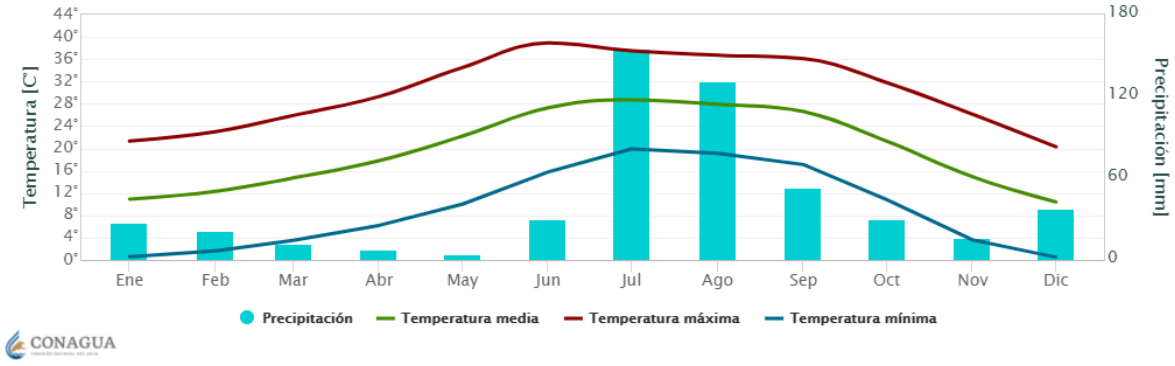

Fuente: Tomado del portal digital del Servicio Meteorológico Nacional (18/12/2024).

Calidad del agua

En 2014, fallas en las instalaciones de la mina Buenavista del Cobre, perteneciente a la empresa Grupo México, en Cananea, Sonora, ocasionaron el derrame de 40,000 metros cúbicos de lixiviados de sulfato de cobre acidulado en el arroyo Tinajas, fluyendo al río Bacanuchi, afluente del río Sonora en el municipio de Arizpe.

El derrame causó la afectación de cuatro cuerpos de agua, entre ellos el río Sonora, principal abastecedor de agua para el municipio de San Felipe de Jesús. Según datos de la Comisión para la Prevención contra Riesgos Sanitarios (COFEPRIS), en términos sociales y económicos implicó

pérdidas para agricultores de la cuenca y daños a la salud de 270 personas de la región. Las concentraciones de cobre, arsénico, aluminio, cadmio, cromo, hierro, manganeso y plomo encontrados a lo largo de los ríos involucrados en el derrame rebasaron los límites establecidos en la Norma Oficial Mexicana NOM 127-SSA1-1994, así como en el estado de la calidad del agua del río previo al derrame (CENAPRED PORTAL).

A ocho años de la catástrofe ambiental, se compartieron los resultados del análisis de orina y sangre realizado a cerca de 1,500 personas en el mes de noviembre del 2021, así como un reporte técnico sobre contaminación ambiental elaborado por el Instituto Nacional de Ecología y Cambio Climático (INECC).

Respecto al primer estudio, se confirmó la presencia de metales pesados en la salud de los pobladores de la región. De acuerdo con las autoridades existe una exposición homogénea y constante a plomo en más del 95% de la población, a arsénico en más del 50% y en cadmio en más del 79%.

Respecto al estudio de contaminación ambiental, se demostró la presencia de aluminio, manganeso, cobalto y niquel en el suelo, derivados de la actuación minera. Esta situación reduce la diversidad de especies, principalmente de insectos, lo cual altera la productividad de los cultivos al hacerlos más propensas a plagas y limitar la polinización de la flora local.

Flora

La información recabada de la Enciclopedia de Municipios y Delegaciones de México (INAFED, 2021), menciona que en el municipio abunda la vegetación de mezquital, matorral subtropical, bosque de encino y pino encino.

Dentro del denominado mezquital, las variedades más características son: palo verde, palo fierro, brea, huisache, entre otros. Mientras que la vegetación de matorral subtropical, las principales variedades son uña de gato, nopal, garambullo, tépame, etc.

Fauna

Al interior del municipio se cuenta con las siguientes especies de animales: anfibios: sapo, sapo verde, rana y sapo toro; reptiles: tortuga de río, cachorón, cachora, víboras de cascabel, boa, iguana de rocas, escorpión grande, culebra, salamanquesa, camaleón, víbora sorda y coralillo; mamíferos: venado cola blanca, puma, lince, nutria, ardilla, zorrillo manchado, murciélago y ratón de campo; aves: tortolita cola corta, lechuza, entre otros (INAFED, 2021).

Características sociodemográficas

Según el Censo de Población y Vivienda del año 2020 elaborado por el Instituto Nacional de Estadística y Geografía (INEGI), el municipio de San Felipe de Jesús cuenta con una población de 369 habitantes que representa el 0.01% del total de la entidad. En términos de sexo, 54.4% son hombres y 45.5%, mujeres.

La Tasa de Crecimiento Media Anual (TCMA) del periodo 2010-2020 es de -0.70%, inferior a la de la entidad (1.01%) y similar a la de la región del Río Sonora (-0.62%), lo que indica el despoblamiento progresivo de los municipios que agrupa.

Figura 3. Población total del municipio de 1990 a 2020

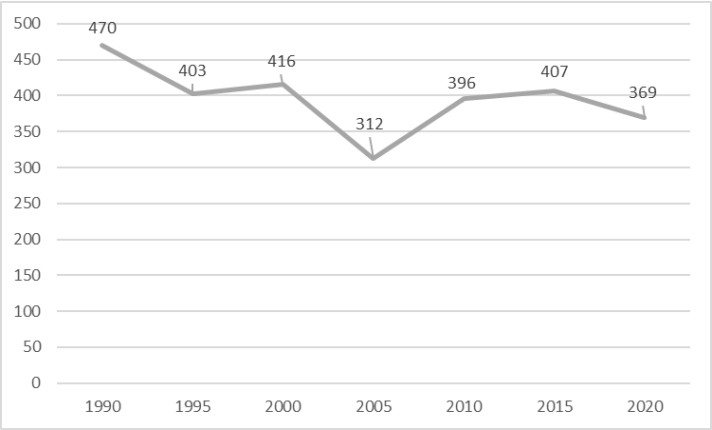

Fuente: Elaboración propia con información de los Censos y Conteos de Población y Vivienda 1990, 1995, 2000, 2005, 2010, 2015 y 2020.

En cuanto a la estructura de edad, 29% de la población son niños y adolescentes entre 0 y 17 años, 15.7% son jóvenes entre 18 y 29 años, 38.5% son adultos entre 30 y 64 años y 16.8% son adultos mayores de 65 años. La edad mediana de la población del municipio es de 36 años; la tasa de fecundidad, es decir el promedio de hijos nacidos vivos, es de 2.34; mientras que la tasa de mortalidad que refiere al porcentaje de hijos fallecidos es de 5.5%.

Respecto a la situación conyugal de la población mayor a 12 años, 59.2% se encuentra casada o unida; 27.2% soltera o nunca unida; y 13.6%, separada, divorciada o viuda.

Figura 4. Pirámide poblacional 2000-2020 y situación conyugal de la población mayor de 12 años

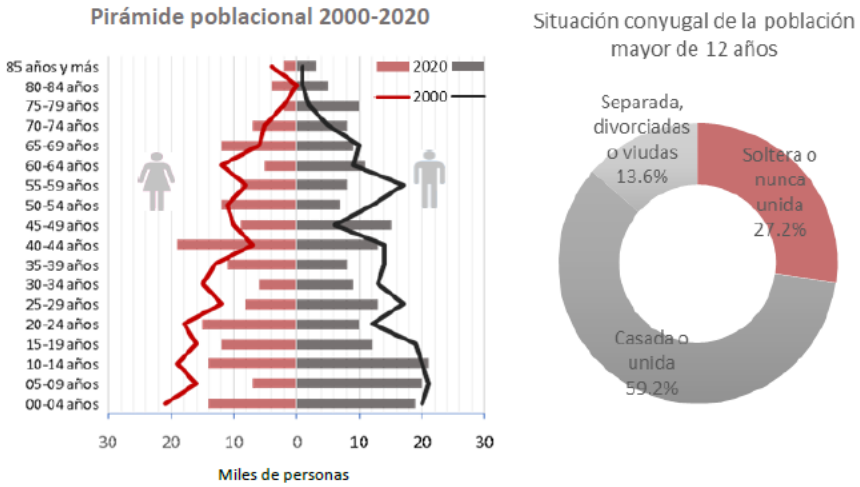

Fuente: Gráfica tomada del portal digital del Consejo Estatal de Población del Gobierno del Estado de Sonora.

En cuestiones de discapacidad[1] se ubicaron a 7 personas con problemas para caminar, subir o bajar; 10 con dificultad para ver aun usando lentes; 3 habitantes con inconvenientes para hablar o comunicarse; 5 personas con imposibilidad de oír, aun usando aparatos auditivos; 3 con incapacidad para vestirse, bañarse o comer; y 4 personas con problemas para recordar o concentrarse.

[1] Entendida como alta dificultad para el desempeño o realización de tareas en la vida cotidiana.

Figura 5. Población del municipio con alguna discapacidad

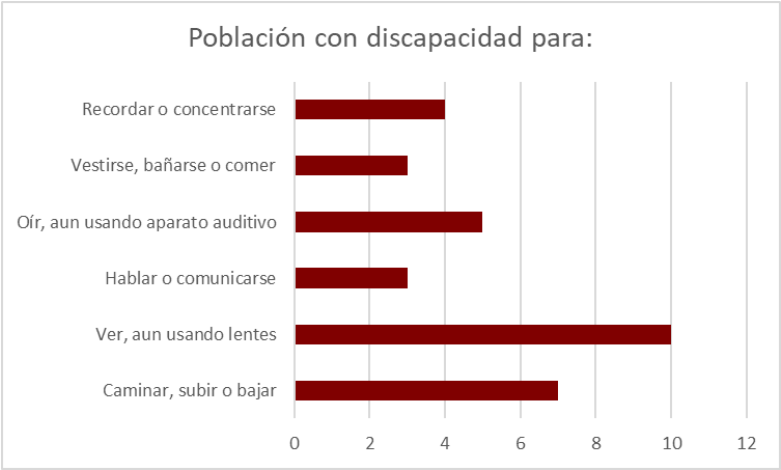

Fuente: Elaboración propia con información del Consejo Estatal de Población del Gobierno del Estado de Sonora.

Respecto a las características educativas de la población, el grado promedio de escolaridad es de 9.5 años; 9.74 para hombres y 9.28 para mujeres; inferior al promedio de la entidad de 10.4 años.

El 45.3% de la población mayor de 15 años cuenta con educación básica completa; 24% con educación media superior; 15% con educación básica trunca; 12% con educación superior; 1.1% sin escolaridad y 3% cuenta con algún posgrado.

En cuanto a la ausencia de educación, el censo muestra que 10.5% de la población entre 3 y 5 años de edad no asisten al jardín de niños; mientras que, de los jóvenes en edad de asistir al bachillerato, 8.3% no lo hacen, cuestión positiva en comparación al 22.8% de la entidad en la misma situación.

Figura 6. Nivel de educación de la población mayor a 15 años e inasistencia escolar por grupos de edad

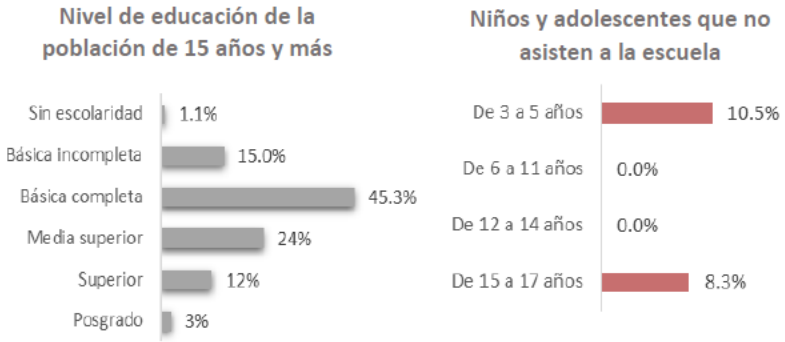

Fuente: Gráfica tomada del portal digital del Consejo Estatal de Población del Gobierno del Estado de Sonora.

Por su parte, la tasa específica de participación económica que indica el porcentaje de la Población Económicamente Activa (PEA) según su nivel de escolaridad, presenta el mayor índice de participación sobre la población que cuenta con educación superior (75%) subsecuentemente se encuentran quienes cuentan con secundaria completa (53.4%), educación media superior (50%), primaria (43.1%) y secundaria incompleta (38.9%).

En San Felipe de Jesús, la tasa específica de participación económica es de 51.6%; 74.1% para hombres y 27.9% para mujeres.

Por otro lado, el municipio, cuenta con índices inmigratorios superiores a los del resto de la región. De la población censada del municipio en 2020, 50 personas son consideradas migrantes mayores de 5 años de edad, que representan el 13.5% del total. De esta cifra, 90% nacieron en la entidad, 2% provienen de otra entidad y 8% de la población son migrantes procedentes de otro país.

Figura 7. Porcentaje de la población nacida fuera del municipio

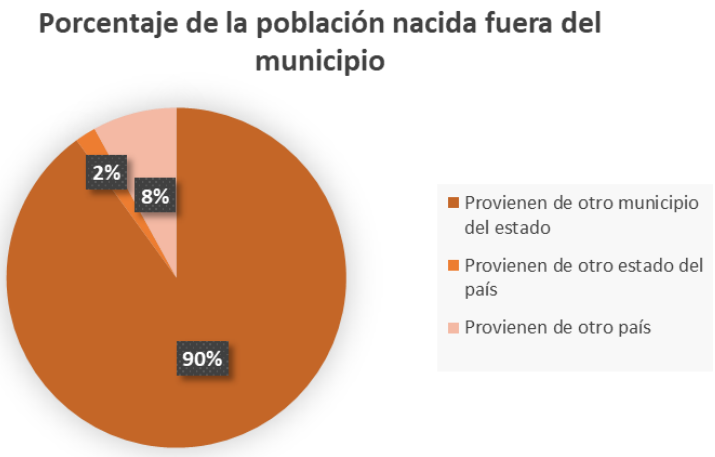

Fuente: Censos de Población y Vivienda 2020, INEGI.

En cuanto a la derechohabiencia a servicios de salud, únicamente el 8.9% de la población declaró no estar afiliada a ninguna institución pública o privada. 24.7% se encuentra afiliada al IMSS, 44% al Instituto de Salud para el Bienestar (antes Seguro Popular), 28.9% al ISSSTESON, 207% al ISSSTE y no se registró población afiliada a alguna otra institución pública o privada.

En el municipio 48.4% de la población es considerada como económicamente inactiva, de ésta 56.1% se dedica a los quehaceres del hogar, 19.4% es estudiante, 9.4% es pensionada o jubilada, 9.4% se dedica a otras actividades no económicas y 5.8% cuenta con alguna limitación física o mental permanente.

Por su parte, 51.6% de la población es económicamente activa, de la cual 73.6% son hombres y 26.4% son mujeres. Asimismo, del total de la PEA, 99.3% se encuentra ocupada, mientras que el restante 0.7% está desocupada.

En cuestión de salarios, en 2020 se identifica que al menos el 67.8% de la población ocupada cuenta con ingresos menores a 2 salarios mínimos, situación negativa al compararse con el año 2010, donde 46.2% de la población vivía en la mencionada situación salarial. Asimismo, se considera que al menos 44.9% de la población se encuentra con un ingreso inferior a la línea de bienestar (CONEVAL).

Por su parte, el grado de marginación del municipio es considerado por el Consejo Nacional de Población (CONAPO) como “muy bajo” y ocupa el lugar 2,161 dentro de los 2,469 municipios que integran el territorio mexicano. Vale decir que, en el año 2010, el CONEVAL ubicaba a 5 personas en situación de pobreza extrema, actualmente no se registra alguna.

Hogares, vivienda y disponibilidad de servicios públicos, bienes y tecnología de información y comunicación

En el municipio existen 124 viviendas particulares habitadas al año 2020, las cuales representan un decremento de 6 unidades con respecto al censo anterior (130 en 2010), cuestión que coincide con la pérdida de población en el mismo periodo. En cuanto al promedio de habitantes por vivienda la cifra sufre una breve reducción de 3.05 en el año 2010 a 2.98 en el año 2020.

Tabla 4. Viviendas particulares habitadas, población total y promedio de habitantes por vivienda

Año	Viviendas particulares habitadas	Población total	Promedio de habitantes por vivienda
2010	130	396	3.05
2020	124	369	2.98

Fuente: Elaboración propia con información de los Censos y Conteos de Población y Vivienda del INEGI, 2010,2015 y 2020.

En la actualidad, el uso de la vivienda particular se distribuye en 43.4% como habitada, 28.3% de uso temporal y 28.3% deshabitada. En contraste, el censo del 2010 indica que ha habido un importante aumento de vivienda de uso temporal (15.9% vs 28.3%), así como un preocupante incremento de vivienda deshabitada (10.2% vs 28.3), mientras que las viviendas habitadas continuamente han sufrido un decremento importante (73.8% vs 43.4%).

Del total de viviendas particulares habitadas, 99.2% dispone de energía eléctrica, 100% cuenta con agua entubada, 99.2% cuenta con escusado o sanitario, 99.2% tiene drenaje y 84.1% cuenta con tinaco. Asimismo, 21.5% de población vive en algún nivel de hacinamiento, cuestión que se ha quedado prácticamente estática en comparación al 2010, cuando 22.8% de la población vivía en esta condición.

En cuanto a la existencia de tecnologías de información y comunicación, existe un aumento tanto en la necesidad de éstas como en su disposición. En contraste al Conteo de Población y Vivienda 2015 (INEGI), las viviendas que cuentan con servicio de internet pasaron de representar el 12.2% al 20.6% en el año 2020; en cuanto a disponer de una computadora, tablet o laptop se pasó de 28.8% a 32.5%; y respecto a telefonía celular, se pasó de 82% en 2015 a 89.7% de las viviendas que cuentan con al menos uno.

Situación económica

Según los Censos Económicos 2019, la población ocupada del municipio se encuentra laborando en un 50.4% en el sector terciario, 14.9% en el secundario y 34.7% en el primario.

De este último sector se derivan las actividades tradicionales de la población: la agricultura y ganadería. De la primera, la producción se concentra en forrajes y alfalfa que componen el principal insumo alimenticio para la ganadería del municipio. En 2023, la producción agrícola alcanzó los 20.3 millones de pesos (SAGARHPA, 2021), la más alta registrada en los últimos 20 años y superando a la producción pecuaria (9.1 M).

Figura 8. Distribución del valor de la producción agrícola por tipo de cultivo, 2020

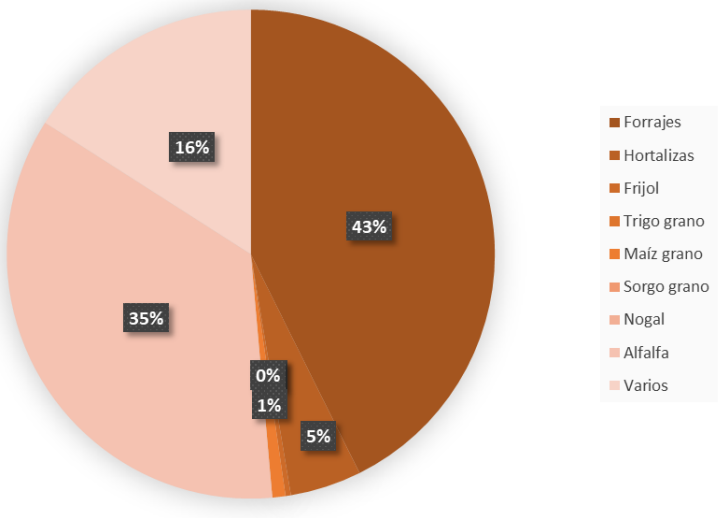

Fuente: Elaboración propia con datos de los distritos de desarrollo rural, SAGARHPA.

Figura 9. Valor de la producción agrícola (millones de pesos) y producción total (toneladas) de San Felipe de Jesús, 2003-2023

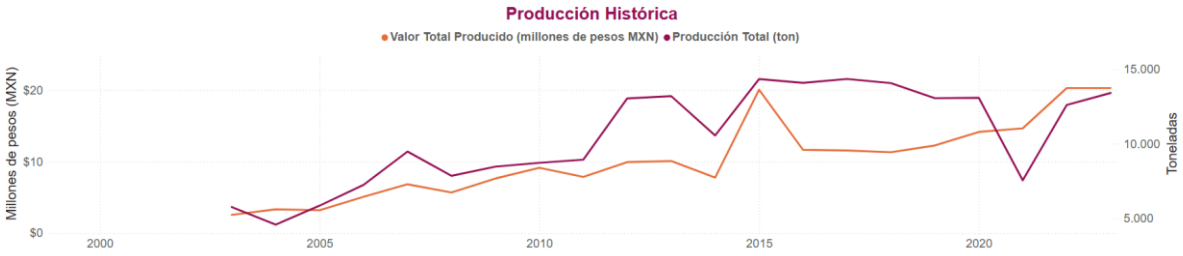

Fuente: Tomado del portal de datos abiertos, SAGARHPA, Estado de Sonora.

En cuanto a la producción pecuaria, San Felipe de Jesús obtuvo un valor de 9.1 millones de pesos en el año 2023 (SAGARHPA, 2024), producción en crecimiento respecto al año anterior, pero aún por debajo de los valores obtenidos previo al derrame de lixiviados en el río Sonora en el año 2014.

Figura 10. Valor de la producción pecuaria (millones de pesos) y volumen total producido (toneladas) del municipio de San Felipe de Jesús, 2006-2023

Fuente: Tomado del portal de datos abiertos, SAGARHPA, Estado de Sonora.

Situación del equipamiento

Educación

San Felipe de Jesús cuenta con servicios educativos de nivel básico. Los equipamientos que brindan estos servicios se componen por un centro preescolar, una primaria y una secundaria.

Tabla 5. Equipamiento escolar

EQUIPAMIENTO ESCOLAR						
	Preescolar		Primaria		Telesecundaria	
	Plantel	Alumnos	Plantel	Alumnos	Plantel	Alumnos
San Felipe de Jesús	1	17	1	30	1	17

Fuente: Elaboración propia con información del Sistema de Información y Gestión Educativa, SEP.

Salud

En cuanto a los servicios de salud públicos, al interior de la cabecera municipal se ubica una clínica de salud rural que brinda atención médica básica sin servicios de hospitalización. Cabe señalar que el hospital comunitario más cercano se encuentra a 81 kilómetros de la cabecera municipal, en la demarcación de Ures.

Cultura, recreación y deporte

El municipio también cuenta con dos campos públicos de beisbol, un parque de barrio, una plaza cívica, un espacio cerrado para eventos, así como el centro recreativo de El Jojobal.

Servicios públicos

Para valorar el estado de los servicios públicos, se generó una consulta ciudadana a través de una encuesta en línea. El ejercicio obtuvo la participación de 49 personas que otorgó un nivel de confianza de 90% y un margen de error del 11% a las respuestas obtenidas.

Servicio de agua

Según la encuesta elaborada, el 95.5% de la población considera que el servicio de agua va de regular a excelente, mientras que únicamente el 4.5% lo considera malo. Esta percepción se mantiene prácticamente igual en relación al mismo sondeo llevado a cabo en 2021, no obstante que existe una mayor proporción de la población (7%) que considera que el servicio ha pasado de bueno y muy bueno a regular.

Figura 11. Percepción del servicio de agua

Pregunta: Del 1 al 5 (1 como mínimo y 5 como máximo), ¿qué tan satisfecho se siente con el servicio de agua?

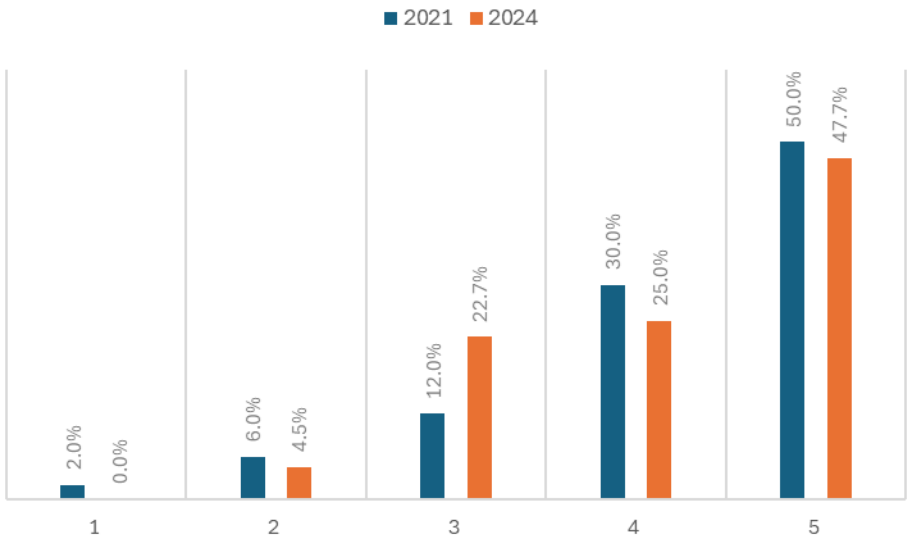

Fuente: Elaboración propia con información de las encuestas virtuales "Consulta ciudadana para la elaboración del PMD 2021-2024" y "Consulta ciudadana para la elaboración del PMD 2024-2027".

En cuanto al costo de la tarifa de agua potable, la mayor parte de la gente cree que su cobro es justo (84.1%), 13.6% considera que es barata y 2.3% que es cara. En contraste al sondeo del 2021, menos población se considera en los extremos de barata y cara, y un mayor número de personas considera que la tarifa es "justa" (68.8% en 2021 y 84.1% en 2024).

Figura 12. Percepción del costo de la tarifa de agua

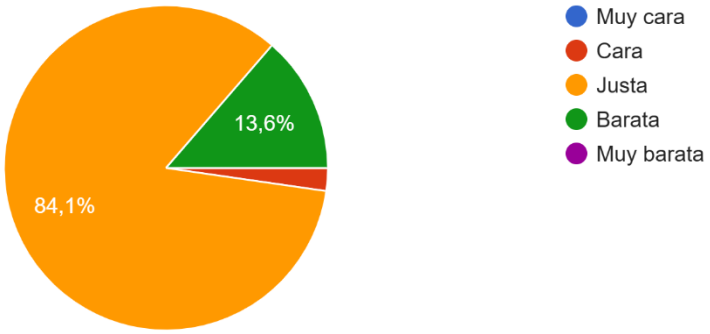

Fuente: Elaboración propia con información de la encuesta virtual "Consulta ciudadana para la elaboración del PMD 2024-2027".

Recolección de basura

Respecto al servicio de recolección de basura, 100% de la población discurre que la labor va de regular a excelente, en contraste al sondeo anterior, donde 8% consideró la existencia de una mala gestión de los residuos sólidos en 2021.

Figura 13. Percepción del servicio de recolección de basura

Pregunta: Del 1 al 5 (1 como mínimo y 5 como máximo), ¿qué tan satisfecho se siente con el servicio de recolección de basura?

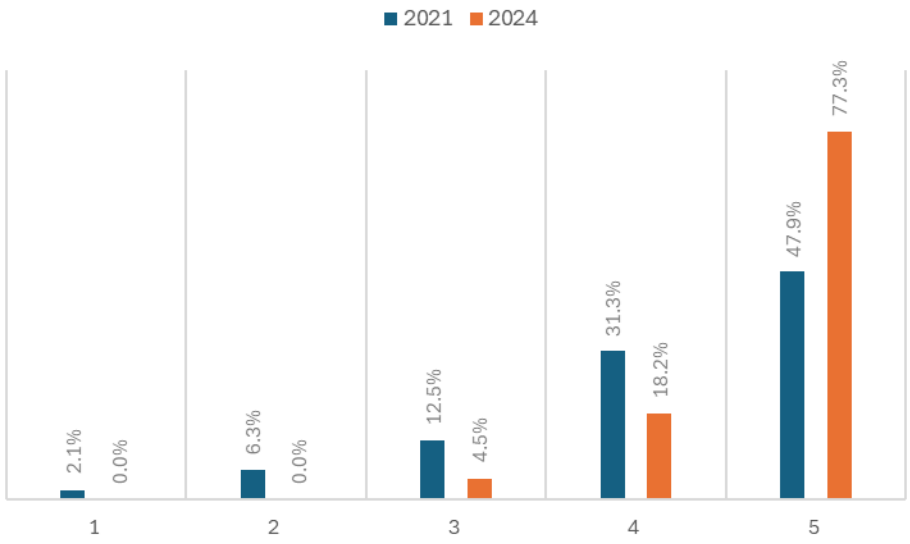

Fuente: Elaboración propia con información de las encuestas virtuales "Consulta ciudadana para la elaboración del PMD 2021-2024" y "Consulta ciudadana para la elaboración del PMD 2024-2027".

Alumbrado público

El alumbrado público del municipio también cuenta con calificaciones en su mayoría positivas: el 100% de la población considera que el servicio va de regular a excelente, con mejoras significativas en su percepción.

Figura 14. Percepción del servicio de alumbrado público

Pregunta: Del 1 al 5 (1 como mínimo y 5 como máximo), ¿qué tan satisfecho se siente con el servicio de alumbrado público?

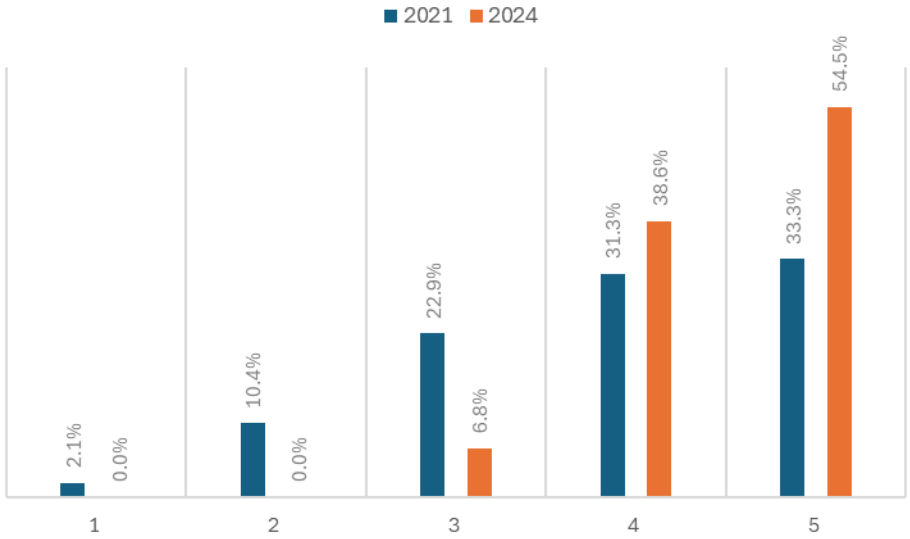

Fuente: Elaboración propia con información de las encuestas virtuales "Consulta ciudadana para la elaboración del PMD 2021-2024" y "Consulta ciudadana para la elaboración del PMD 2024-2027".

Caminos y pavimentación

La calificación para este rubro, aunque mantiene una percepción positiva, presenta una tendencia hacia la baja. En este sentido, 38.6% de la población encuestada considera los caminos y su pavimentación en estado excelente, 27.3% los considera en buen estado, 25% en estado regular, 2.3% en mal estado y 6.8% en pésimo estado. Sobre estos últimos rubros contrasta la percepción negativa registrada en 2021 cuando 20.8% consideró los caminos y pavimentación en estado regular, 4.2% en mal estado y 2.1% en pésimo.

Figura 15. Percepción del estado de caminos y pavimentación

Pregunta: Del 1 al 5 (1 como mínimo y 5 como máximo), ¿qué tan satisfecho se siente con el estado de los caminos y la pavimentación?

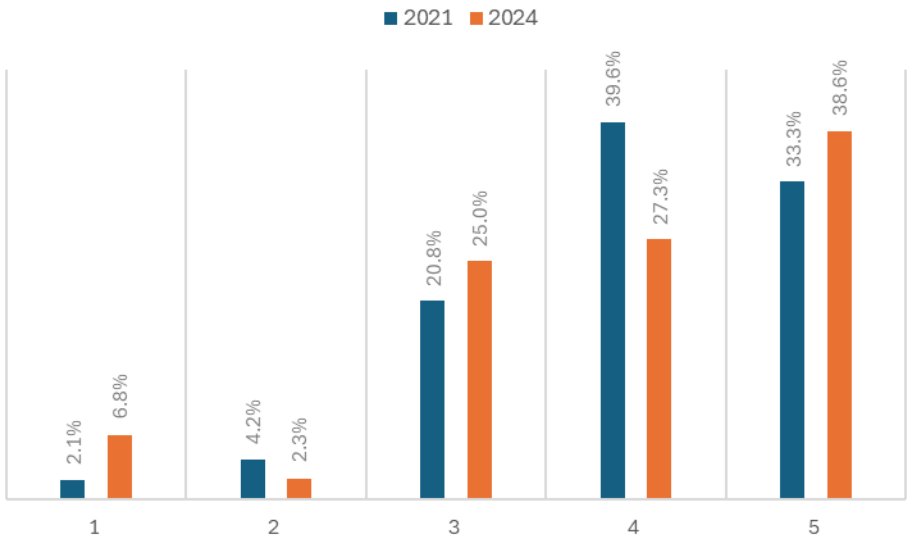

Fuente: Elaboración propia con información de las encuestas virtuales "Consulta ciudadana para la elaboración del PMD 2021-2024" y "Consulta ciudadana para la elaboración del PMD 2024-2027".

Espacio público

La calidad y disponibilidad de áreas verdes cuenta con una calificación en su mayoría positiva, así como una tendencia hacia su mejoramiento. Mientras que quienes consideran los espacios públicos de mala o pésima calidad se mantienen en proporción entre el sondeo del 2021 y 2024; la proporción de población que considera el excelente estado de estos espacios a crecido.

Figura 16. Percepción sobre disponibilidad de áreas verdes y espacio público

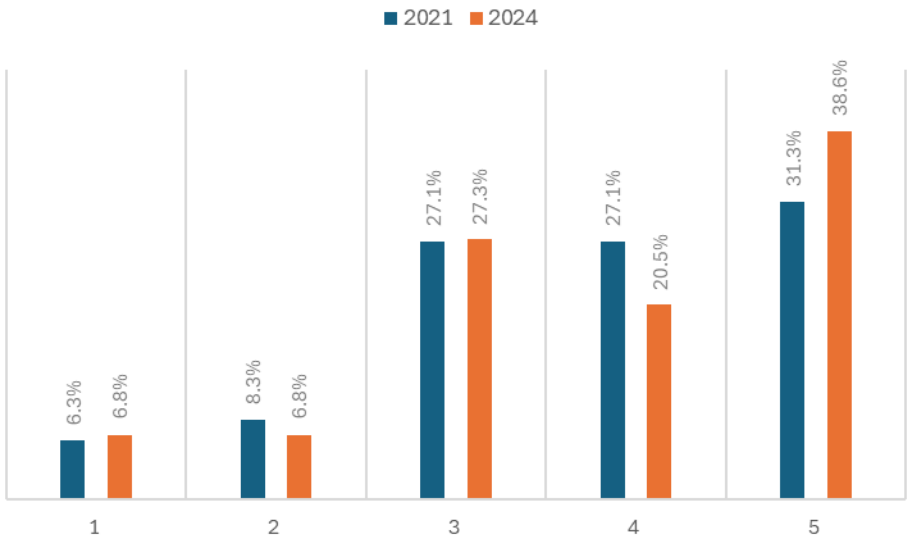

Fuente: Elaboración propia con información de las encuestas virtuales “Consulta ciudadana para la elaboración del PMD 2021-2024” y “Consulta ciudadana para la elaboración del PMD 2024-2027”.

En cuanto a la limpieza del espacio público, panteones, calles y jardines, 59.1% de la población expresó que es excelente, 18.2% que es buena, 15.9% que es regular, 4.5% que es mala y 2.3% que es pésima.

Figura 17. Percepción sobre limpieza del espacio público

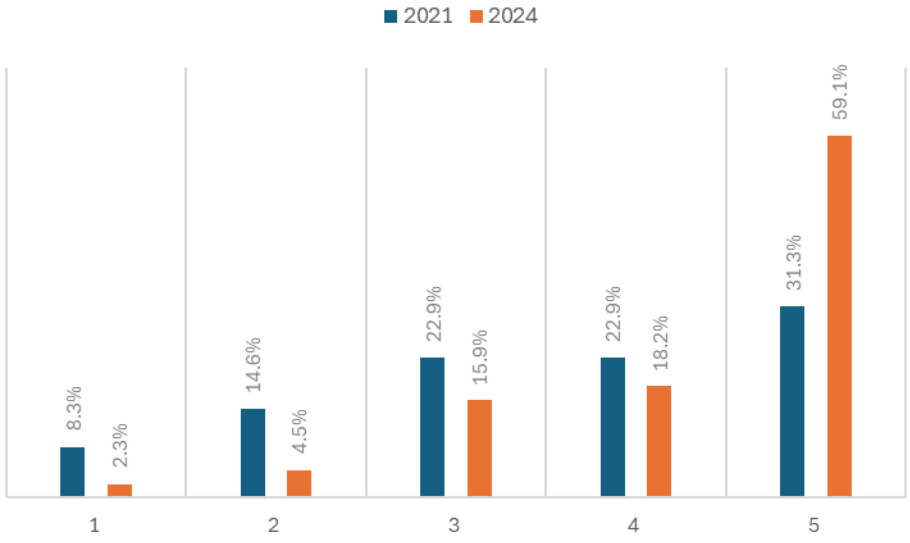

Fuente: Elaboración propia con información de las encuestas virtuales “Consulta ciudadana para la elaboración del PMD 2021-2024” y “Consulta ciudadana para la elaboración del PMD 2024-2027”.

Seguridad Pública

De acuerdo con la percepción de seguridad, la mayor parte de la población considera que es seguro vivir en el pueblo: 29.2% calificó como muy seguro el pueblo, 29.2% como seguro, 29.2 como ni seguro ni inseguro, 8.3% como inseguro y 4.2% como muy inseguro.

Figura 18. Percepción de seguridad

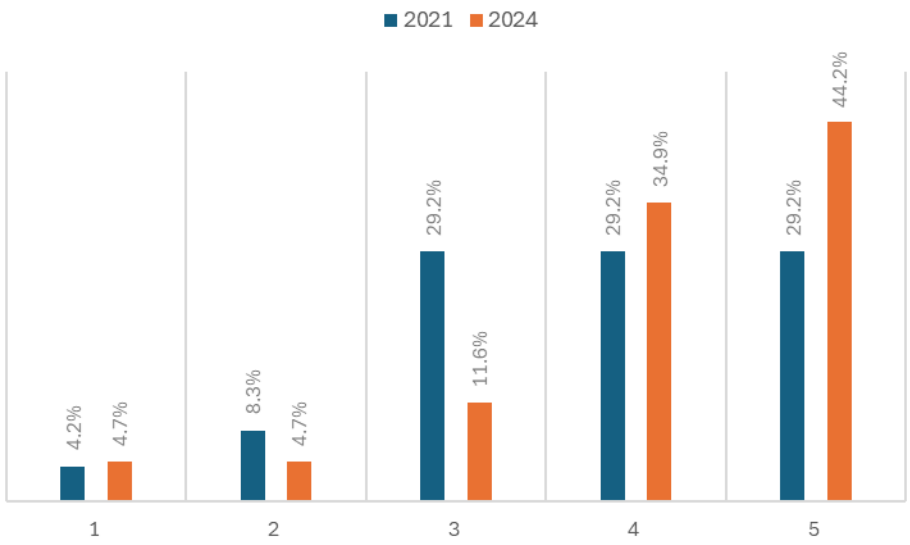

Fuente: Elaboración propia con información de las encuestas virtuales "Consulta ciudadana para la elaboración del PMD 2021-2024" y "Consulta ciudadana para la elaboración del PMD 2024-2027".

Áreas de oportunidad según sondeo

El sondeo, como instrumento de retroalimentación, también ofrece una mirada más específica sobre aquellos aspectos a mejorar respecto al periodo administrativo anterior. Al respecto, se incluyó la pregunta "¿Qué aspectos considera que debe mejorar la administración municipal 2024-2027 respecto al periodo anterior?"

En primer lugar, destacó la necesidad de ayuntamiento más inclusivo y equitativo en sus decisiones, así como una mejor coordinación en sus ejecuciones; en segundo lugar, aparece la seguridad pública como pendiente constante; en tercer lugar aparecen 2 rubros a mejorar: la iniciativa a más programas para jóvenes (deporte, arte y cultura, etc) y solucionar el problema del vado del río. En cuarto lugar, se presentan algunos aspectos interrelacionados como son el mejor ejercicio de los recursos públicos, la necesidad de más obra pública, la pavimentación de calles y la asistencia social. Por último, se consideran aspectos a mejorar al apoyo a la vivienda y la comunicación social del ayuntamiento.

Figura 19. Áreas de oportunidad según sondeo

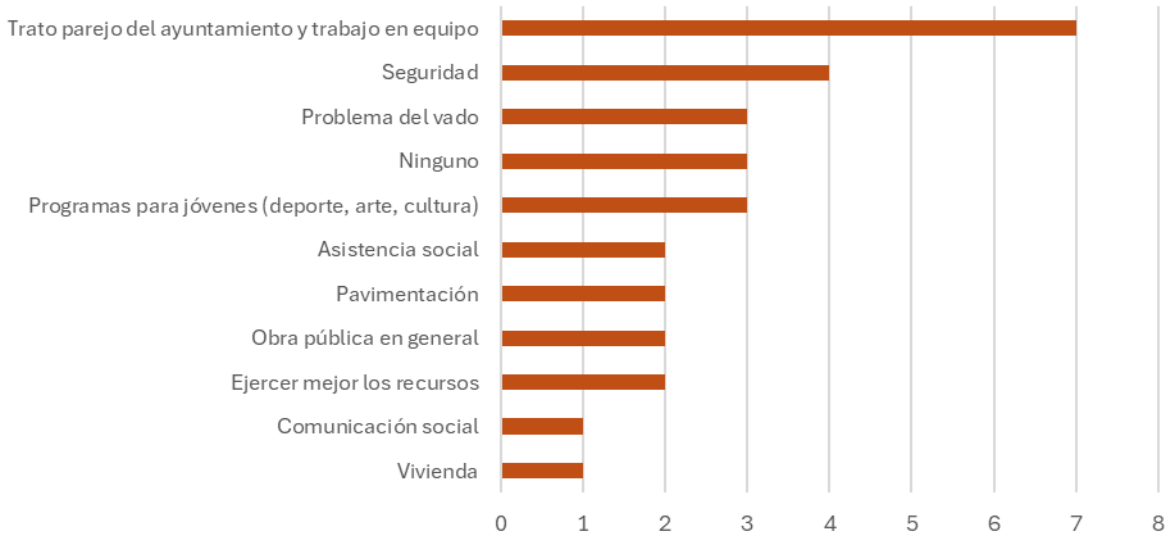

Fuente: Elaboración propia con información de la encuesta virtual "Consulta ciudadana para la elaboración del PMD 2024-2027".

Fortalezas de la administración según sondeo

Por su parte, las fortalezas de la administración según el sondeo del 2024 se presentaron en el reconocimiento de los beneficios obtenidos a través de la asistencia social que ha brindado el municipio, especialmente a adultos mayores. En segundo lugar, se identificaron como fortalezas al liderazgo y el trabajo en equipo dentro del ayuntamiento, así como al apoyo equitativo e inclusivo que se ha logrado, en contraste a lo que se consideró como un área de oportunidad en el apartado anterior; en tercer lugar, se consideraron como fortalezas al apoyo a la vivienda, la atención ciudadana y el apoyo al sector agropecuario; por último, se consideraron como aspectos positivos al servicio de recolección de basura, al servicio de salud, al empleo otorgado dentro del ayuntamiento y a la educación.

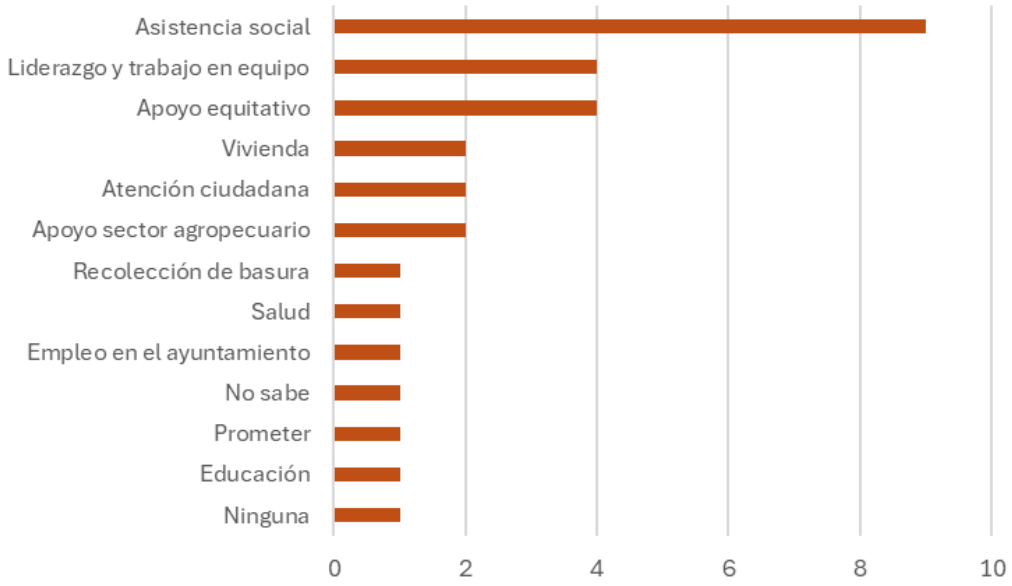

Fuente: Elaboración propia con información de la encuesta virtual "Consulta ciudadana para la elaboración del PMD 2024-2027".

FODA Social

Fortalezas

- Muy bajos grados de marginación
- Servicios urbanos cubiertos casi en su totalidad y con una percepción de alta calidad
- No hay zonas de riesgo habitadas
- Alta asistencia educativa
- No hay registro de pobreza extrema
- Fuerte asistencia social por parte del ayuntamiento
- Percepción positiva de calidad y limpieza de espacios públicos

Oportunidades

- Posibilidad de crear servicios para la gente que inmigra en edad no productiva
- Existencia de originarios del municipio en buena situación económica viviendo en EUA
- Municipio forma parte de la Zona Económica Especial del Río Sonora

Debilidades

- Decrecimiento poblacional; alta emigración de población joven
- Pocas opciones de empleo
- 67.8% cuenta con ingresos inferiores a los 2 salarios mínimos
- Vivienda abandonada en crecimiento
- Poca población con servicio a internet
- Poca diversificación de actividades culturales y deportivas
- Incomunicación vial ante crecidas del río Sonora
- Poco arraigo de los jóvenes por la educación
- Agotamiento de tierras del fundo legal
- Contaminación del aire por quema de basurero
- Falta de mantenimiento a canales de riego, alcantarillado, laguna de oxidación
- Seguridad y señalización vial deficiente
- Existen solares sin mantenimiento; peligro de incendios y riesgos sanitarios

Amenazas

- La pandemia por COVID creó nuevas necesidades de servicios digitales y comunicación
- Contaminación del agua
- Pérdida del patrimonio construido por el abandono progresivo de vivienda
- Percepción sobre caminos y pavimentos y calidad y costo del servicio de agua con tendencia a la baja

FODA Económico

Fortalezas

- Perseverancia en las actividades productivas tradicionales
- Recuperación de producción agropecuaria a niveles anteriores al derrame de lixiviados en el río Sonora

Oportunidades

- Demanda de proveedores locales por parte de minera Grupo México
- Cadenas productivas que demandan productos regionales (leche, queso, chiltepín, bacanora, etc.)
- Cercanía al enorme mercado estadounidense: consumo de productos artesanales
- Potencial de desarrollo turístico

Debilidades

- No hay producción agrícola para consumo humano; se importan productos de otras regiones
- Patrón de cultivo sólo para consumo pecuario
- Poca diversificación de actividades productivas
- Oferta turística insuficiente
- Población en edad productiva emigra

Amenazas

- Se acabaron los apoyos al campo desde 2018
- Alzas en costos de producción agrícola

V. EJE ESTRATÉGICO 1: GOBIERNO EFICIENTE Y HONESTO

1.1. Objetivo: Garantizar la eficiencia y eficacia en el manejo de la Hacienda Municipal.

1.1.1. Estrategia: Implementar una estructura contable armonizada con los requerimientos y lineamientos promulgados por el Consejo Nacional Contable y la Ley de Contabilidad Gubernamental; así como una operación de los recursos basada en el método del Presupuesto Basado en Resultados y la Evaluación del Desempeño.

Líneas de acción:

1.1.1.1. Llevar a cabo acciones que incrementen los ingresos propios por concepto de impuestos, derechos, licencias, productos, contribuciones de mejora y aprovechamientos.

1.1.1.2. Priorizar y optimizar a través de la utilización de herramientas de planeación y presupuestación estratégicas.

1.1.1.3. Preparar y capacitar a los servidores públicos involucrados en las labores presupuestarias, especialmente en lo que respecta a la evaluación del desempeño.

1.1.1.4. Evaluar los programas presupuestarios.

1.1.1.5. Aplicar la estructura programática emitida por el Consejo Nacional de Armonización Contable y asignar los recursos con base en los resultados alcanzados por los programas presupuestarios.

1.2. Objetivo: Combatir la corrupción mediante la promoción de la transparencia y una actitud servicial hacia los ciudadanos.

1.2.1. Estrategia: Implementar un modelo de control interno y administración de riesgo en la administración municipal, así como cumplir en tiempo y forma con las obligaciones comunes y específicas aplicables.

Líneas de acción

1.2.1.1. Contar con medios de control interno a partir de auditorías internas implementadas en el órgano de control y evaluación gubernamental del Ayuntamiento conforme el plan anual de auditorías.

1.2.1.2. Darle seguimiento a las recomendaciones y observaciones que tengan como resultados de las auditorías internas.

1.2.1.3. El titular del Sistema de evaluación del desempeño y/o titular del Órgano de Control y Evaluación Gubernamental lleven a cabo la revisión en la Plataforma Nacional de Transparencia para que la información este cargada en tiempo y forma conforme la aplicabilidad de esta.

1.2.1.4. El Titular del Órgano de Control y Evaluación Gubernamental podrá imponer las medidas de control interno que considere pertinente para cumplir con la estrategia enmarcada en el punto 1.2.1 del presente plan municipal de desarrollo.

1.2.1.5. Actualizar la reglamentación municipal, considerando las modificaciones a la constitución del estado, a las leyes que de ella emanen, como la ley de gobierno y administración municipal, ley estatal de responsabilidades, entre otras; con el fin de tener el marco normativo vigente y oportuno en sus modificaciones.

1.2.1.6. Conformar un área responsable de implementar un Sistema de Evaluación del Desempeño.

1.2.1.7. Generar información financiera en tiempo real, registrando y capturando los movimientos contables en tiempo y forma.

1.2.1.8. Manejar encuestas de satisfacción para verificar la atención brindada al usuario en las dependencias del gobierno municipal, con el fin de mejorar la atención de calidad; así como implementar un modelo de actuación para los servidores públicos responsables de atender a la ciudadanía.

1.2.1.9. El titular del Órgano de Control y Evaluación Gubernamental implementará capacitaciones por lo menos una vez al año con el fin de utilizar las autoevaluaciones, gestión y tratamiento de los riesgos internos de la institución.

1.2.1.10. Conformar el Comité de adquisiciones, arrendamientos y servicios del municipio, en atención al artículo 223 de la Ley de Gobierno y administración Municipal, para evitar corrupción en la contratación de servicios y arrendamientos que se efectúen en las dependencias o en la contratación de las obras públicas.

1.2.1.11. Difundir los valores institucionales a través del código de ética y conducta de los servidores públicos mismos que se retoman en el presente plan municipal de desarrollo.

1.2.1.12. Atender en tiempo y forma todas las solicitudes de información presentadas por la ciudadanía ante el ayuntamiento.

1.2.1.13. Conformar la unidad de transparencia y nombrar a un enlace municipal de transparencia con el objeto de promover y atender las obligaciones en materia de transparencia, así como recabar y publicar la información en el portal municipal de transparencia en coordinación con todas las dependencias del gobierno municipal.

1.2.2. **Estrategia:** Aplicar sanciones administrativas a los servidores públicos que incumplan con su labor.

Líneas de acción:

1.2.2.1. Vigilar la evolución del patrimonio de los servidores públicos.

1.2.2.2. Atender y concretar las líneas de acción del presente plan municipal de desarrollo.

1.2.2.3. Implementar la investigación y sustanciación en los casos aplicables con la finalidad de determinar responsabilidades administrativas en contra de los servidores públicos.

1.2.2.4. Aplicar las sanciones previstas en la Ley Estatal de Responsabilidades, Reglamento Interno del ayuntamiento, Código de ética y conducta y aquella normatividad aplicable.

1.2.3. **Estrategia:** Fomentar la participación ciudadana y el desarrollo administrativo para fortalecer las capacidades institucionales.

Líneas de acción:

1.2.3.1. Actualizar los manuales de organización y procedimientos de las dependencias y entidades de la Administración Pública Municipal.

1.2.3.2. Atender en tiempo y forma todas las solicitudes de información presentadas por la ciudadanía al Ayuntamiento. Implementar el programa "alcalde 24/7.

1.2.3.3. Llevar a cabo visitas periódicas del alcalde a los distintos barrios del municipio con el fin de escuchar las distintas voces ciudadanas.

1.3. Objetivo: Promover el saneamiento de las finanzas municipales

1.3.1. **Estrategia:** Disminuir el déficit financiero del servicio de abastecimiento público de agua.

Líneas de acción:

1.3.1.1. Promover tarifas diferenciadas por uso de suelo.

1.3.1.2. Regularizar tomas de agua con base en las subdivisiones de vivienda.

1.3.1.3. Gestionar micromedidores por toma de agua.

1.3.1.4. Garantizar el aumento de la tarifa de agua con base en la UMA.

1.3.2. **Estrategia:** Regularizar el cobro de predial urbano y rural

Líneas de acción:

1.3.2.1. Actualizar oportunamente el catastro municipal.

1.3.2.2. Ofrecer facilidades para la regularización.

1.3.2.3. Gestionar convenio con el estado para el cobro del impuesto predial.

VI. EJE ESTRATÉGICO 2: BIENESTAR SOCIAL

2.1. Objetivo: Garantizar el acceso a suelo y vivienda de todos los pobladores del municipio.

2.1.1. Estrategia: Crear reservas territoriales municipales para la construcción de vivienda popular y de interés social, así como fomentar la reocupación de vivienda abandonada.

Líneas de acción:

2.1.1.1. Cuantificar la demanda y definir las condiciones socioeconómicas para el otorgamiento de suelo urbano.

2.1.1.2. Definir los espacios susceptibles al aprovechamiento urbano y un plan maestro para su ocupación ordenada.

2.1.1.3. Crear un padrón de vivienda abandonada con el fin de gestionar su ocupación provisional o permanente por parte de los pobladores que lo requieran.

2.1.1.4. Promover el desarrollo integral de la población vulnerable y con discapacidad

2.1.1.5. Fortalecer las relaciones y gestiones de coordinación y colaboración con el gobierno Federal y Estatal para implementar en el municipio programas sociales.

2.1.1.6. Impulsar un municipio incluyente que atienda el rezago social y promueva el acceso a los servicios básicos.

2.1.1.7. Impulsar programas o proyectos que eliminen las brechas de desigualdad entre hombres y mujeres.

2.1.2. Estrategia: Elaborar un programa municipal de desarrollo urbano y/o de ordenamiento ecológico territorial que defina los espacios susceptibles al crecimiento, mejoramiento y consolidación urbana, así como los espacios destinados a la protección y restauración ambiental y aprovechamiento productivo.

Líneas de acción:

2.1.2.1. Elaborar un instrumento de planeación territorial local que tenga como objetivo reglamentar los usos de suelo al interior del municipio.

2.2. Objetivo: Alcanzar un grado promedio de escolaridad superior a la media estatal.

2.2.1. Estrategia: Promover la continuidad de los estudios de bachillerato y evitar la deserción escolar.

Líneas de acción:

2.2.1.1. Gestionar becas para los alumnos que, por causas socioeconómicas, no pudieran permanecer en la escuela.

2.2.1.2. Promover el talento académico y apoyo a estudiantes universitarios sobresalientes para que continúen con estudios de nivel superior.

2.2.1.3. Implementar campañas sobre adicciones y sexualidad en las escuelas.

2.2.1.4. Promover atención psicológica oportuna a niños y jóvenes.

2.2.1.5. Gestionar la presencia de un maestro para la educación especial en el nivel básico.

2.2.1.6. Apoyar la educación, mediante el programa conectar para ayudar.

2.2.1.7. Dotar de útiles escolares a la población en nivel educativo básico.

2.2.1.8. Fomentar el interés en actividades agrícolas tradicionales por medio de la creación de un huerto comunitario o parcela escolar.

2.2.2. **Estrategia:** Fomentar el ingreso de jóvenes a instituciones de educación superior.
Líneas de acción:

2.2.2.1. Crear un padrón de estudiantes con necesidades de apoyo de manutención para proseguir con sus estudios a nivel superior.

2.2.2.2. Gestionar recursos estatales, federales y/o privados para la creación de una casa del estudiante de San Felipe de Jesús.

2.2.3. **Estrategia:** Difundir actividades culturales y deportivas que refuercen el interés educativo.
Líneas de acción:

2.2.3.1. Crear talleres y exposiciones que fomenten el talento creativo de los niños y jóvenes.

2.2.3.2. Organizar ligas deportivas locales e intermunicipales.

2.2.3.3. Rehabilitación de estadios de beisbol y del parque recreativo de "El Jojobal" con el impulso de actividades deportivas y culturales en su interior.

2.2.3.4. Acondicionamiento del gimnasio municipal.

2.3. Objetivo: Reducir las carencias materiales de la población.

2.3.1. **Estrategia:** Promover y gestionar apoyos en especie y capacitación de trabajo a la población más vulnerable.
Líneas de acción:

2.3.1.1. Promover las "Rondas del Bienestar" en el municipio con el fin de atender de primera mano las necesidades de la población infantil, jóven, adultos, adultos mayores y personas con discapacidad.

2.3.1.2. Continuar con el programa de comidas del adulto mayor.

2.3.1.3. Gestionar el acceso de la población a programas sociales del estado y la federación.

2.3.1.4. Crear convenios con el Instituto de Capacitación para el Trabajo del Estado de Sonora (ICATSON) para capacitaciones en nuevas actividades económicas.

2.3.1.5. Facilitar el apoyo económico por parte de los originarios del municipio en mejores condiciones socioeconómicas, especialmente para aquellos residiendo en los Estados Unidos de América.

2.4. Objetivo: Ofrecer certeza jurídica a los propietarios de vivienda.

2.4.1. **Estrategia:** Regularizar situación jurídica de las propiedades inmuebles.

Línea de acción:

2.4.1.1. Crear un programa de regularización de la propiedad inmobiliaria.

VII. EJE ESTRATÉGICO 3: LA IGUALDAD EFECTIVA DE LOS DERECHOS Y EL ACCESO A SERVICIOS PÚBLICOS DE CALIDAD

3.1. Objetivo: Contribuir a mejorar la calidad de vida de los habitantes del municipio mediante una amplia cobertura en la prestación de los servicios públicos de recolección de basura, limpieza, panteones, rastro, alumbrado público, telecomunicaciones, parques y jardines.

3.1.1. Estrategia: Proporcionar un servicio de recolección de basura suficiente y de calidad.

Líneas de acción:

3.1.1.1. Reparación y mantenimiento de la unidad recolectora existente

3.1.1.2. Reparación y mantenimiento de los contenedores de basura

3.1.2. Estrategia: Proporcionar un servicio de limpia y rastro municipal.

Líneas de acción:

3.1.2.1. Realización de una campaña de limpieza por elementos del personal de la Dirección Municipal de Servicios Públicos.

3.1.2.2. Limpieza y/o mantenimiento del basurón público municipal.

3.1.2.3. Crear un programa de reciclaje y separación de basura.

3.1.3. Estrategia: Contar con un panteón digno.

Líneas de acción:

3.1.3.1. Mantenimiento y conservación del panteón municipal.

3.1.3.2. Creación de un plan maestro del panteón municipal que defina y ordene su utilización.

3.1.4. Estrategia: Limpieza en parques y jardínes

Líneas de acción:

3.1.4.1. Llevar a cabo un programa de reforestación y forestación del espacio público.

3.1.4.2. Mantenimiento y conservación de los estadios deportivos del municipio.

3.1.4.3. Mantenimiento y conservación de plazas y canchas públicas.

3.1.5. Estrategia: Garantizar el servicio de alumbrado público a toda la población.

Líneas de acción:

3.1.5.1. Mantenimiento, conservación y ampliación de la red de alumbrado público municipal.

3.1.6. Estrategia: Garantizar la conectividad a internet.

Línea de acción:

3.1.6.1. Gestionar la instalación de antena para servicio de internet por parte de la Comisión Federal de Electricidad (CFE).

3.2. Objetivo: Garantizar el acceso oportuno a los servicios integrales de salud.

3.2.1. Estrategia: Promover la prevención y atención oportuna de salud a la población.

Líneas de acción:

3.2.1.1. Gestionar los servicios de hospitalización en el centro de salud (véase el compromiso del gobierno estatal por dotar de un hospital a la región del Río Sonora).

3.2.1.2. Contar con un servicio de ambulancia digno.

3.2.1.3. Brindar apoyo de viáticos a la población con familiares en hospitales.

3.2.1.4. Brindar brigadas de salud para los habitantes del municipio.

3.2.1.5. Crear campañas de esterilización de mascotas.

3.3. Objetivo: Contribuir a un desarrollo urbano socialmente justo mediante la ejecución de obras de infraestructura y equipamiento urbano.

3.3.1. Estrategia: Rehabilitación de los caminos vecinales y repavimentación de vialidades seleccionadas.

Líneas de acción:

3.3.1.1. Pavimentación de calles

3.3.1.2. Rehabilitación de calles con recarpeteo.

3.3.1.3. Rehabilitación de calles con bacheo.

3.3.1.4. Rehabilitación de caminos rurales.

3.3.2. Estrategia: Rehabilitación, mantenimiento, conservación y construcción de equipamiento urbano.

Líneas de acción:

3.3.2.1. Mantenimiento, construcción y conservación de espacios públicos.

3.3.2.2. Llevar a cabo soluciones de tránsito por medio del ordenamiento vial, construcción de guarniciones y señalización adecuada.

3.3.2.3. Reparación, mantenimiento y adquisición de maquinaria para obras públicas.

3.3.3. Estrategia: Rehabilitación y ampliación de la red de drenaje y saneamiento.

Líneas de acción:

3.3.3.1. Elaborar un diagnóstico para identificar los espacios sujetos a la rehabilitación y ampliación de la red de drenaje.

3.3.3.2. Destinar recursos propios y gestionar recursos estatales, federales y del sector privado para la ampliación y rehabilitación del servicio de drenaje.

3.3.3.3. Rehabilitar la laguna de oxidación.

3.4. Objetivo: Garantizar la conectividad vial de la cabecera municipal todo el año.

3.4.1. Estrategia: Materializar las obras previstas para garantizar la conectividad vial.

Líneas de acción:

3.4.1.1. Gestionar recursos estatales y federales para la construcción de un puente vehicular que dé acceso a la cabecera municipal.

3.4.1.2. Contar con un proyecto ejecutivo actualizado del puente vehicular.

3.4.1.3. Mantener el vado actual en condiciones óptimas para el cruce vehicular.

VIII. EJE ESTRATÉGICO 4: DESARROLLO ECONÓMICO, SEGURIDAD Y SUSTENTABILIDAD

4.1. Objetivo: Promover un desarrollo económico local de manera incluyente y sustentable.

4.1.1. Estrategia: Aprovechar el potencial turístico del municipio.

Líneas de acción:

4.1.1.1. Crear una cámara de turismo incluyente y sustentable.

4.1.1.2. Crear un padrón de casas de huéspedes que reciban a la población turista.

4.1.1.3. Presentar un catálogo de actividades turísticas del municipio y/o la región.

4.1.1.4. Gestionar recursos para la construcción y resguarde de activos turísticos materiales del municipio.

4.1.1.5. Promover festivales culturales y/o gastronómicos o ser sede de eventos para la promoción del municipio, especialmente sobre sus actividades agropecuarias tradicionales.

4.1.1.6. Crear un módulo de atención turística.

4.2. Objetivo: Fortalecer el desarrollo agrícola y pecuario del municipio

4.2.1. Estrategia: Estimular acciones orientadas al desarrollo económico, así como la diversificación de los productos.

Líneas de acción:

4.2.1.1. Crear cadenas de valor con las empresas mineras de la región.

4.2.1.2. Gestionar apoyos estatales, nacionales y privados que promuevan la diversificación de los productos agrícolas.

4.2.1.3. Fomentar el emprendedurismo empresarial por medio de programas destinados a mujeres y jóvenes.

4.2.1.4. Rehabilitación, modernización y tecnificación de la infraestructura destinada al riego, particularmente de la unidad de riego “El Jojobal” y “El Llano”.

4.2.1.5. Rehabilitar y mantener los represos.

4.2.1.6. Implementar apoyos para la agricultura de traspatio, así como huertos comunitarios.

4.2.1.7. Promover la localización de agroindustria, así como actividades industriales que le añadan valor a los productos agrícolas y pecuarios de la región (dulces, bacanora, salsas de chiltepín, etc.).

4.3. Objetivo: Garantizar el estado de derecho para la promoción de un desarrollo económico competitivo e incluyente.

4.3.1. Estrategia: Contar con un cuerpo policiaco capacitado, capaz y efectivo, en permanente contacto con el ciudadano.

Líneas de acción:

4.3.1.1. Contar con una vigilancia más activa, con atención oportuna a los reportes ciudadano.

4.3.1.2. Realizar continuas capacitaciones a los cuerpos policiacos, en especial las relacionadas al respeto de los derechos humanos.

4.3.1.3. Contar con el equipo necesario para llevar a cabo las labores de seguridad y paz.

IX. COMPROMISOS ESPECÍFICOS DEL MUNICIPIO DE SAN FELIPE DE JESÚS CON BASE EN EL PLAN ESTATAL DE DESARROLLO 2022-2026

Eje	Objetivo	Tema	Compromiso/Subtema	N° Compromiso
La igualdad efectiva de derechos para todas y todos				
	Sostenibilidad del Desarrollo Regional			
		Desarrollo Económico Inclusivo		
			Cooperativas del Río Sonora	174
			Resolver los Problemas Ocasionados por el Derrame en el Río Sonora	230
El presupuesto social más grande de la historia				
	Salud Universal			
		Salud Incluyente		
			Hospital en el Río Sonora	286
Un Gobierno para todos y no para unos cuanntos				
	Educación, cultura, juventud, deporte, ciencia, tecnología y sociedad digital.			
		Difusión Cultural		
			Promocionar las Fiestas para cada Pueblo de la Sierra	106

Fuente: Cuadro proporcionado por la Coordinación de Planeación y Comisiones del Consejo Consultivo para el Plan Estatal de Desarrollo 2021-2027.

X. COMPROMISOS GENERALES DE CAMPAÑA CON COBERTURA ESTATAL CON BASE EN EL PLAN ESTATAL DE DESARROLLO 2022-2026

Eje	Objetivo	Tema	Compromiso/Subtema	N° Compromiso	Tipo Compromiso
Un Gobierno para todos y no para unos cuantos					
	Educación, cultura, juventud, deporte, ciencia, tecnología y sociedad digital.				
		Educación Incluyente y de Calidad			
			Transformando Sonora desde las Escuelas	244	Acción
			Educación de Calidad	302 309	Acción
			Salud Emocional en la Educación	319	Programa
			Planteles Dignos y Equipados	324	Proyecto
			Educación Universal Inclusiva, Pública, Gratuita y Laica	3221	Acción
			Combate a los Rezagos de Inclusión y Cobertura	310	Acción
			Tronco Común en la Educación Media Superior	313	Programa
			Competencias Interuniversitarias	289	Proyecto
			Becas de Posgrado	290	Acción
			Educación Digital	326	Acción
			Educación para la Vida	329	Acción
			Educación con Enfoque Regional	266	Acción
			Ampliación del Sistema Estatal de Becas	325	Acción
			Escuela de Tiempo Completo	270	Acción
			Planes de Estudio con Prioridad en las Ciencias, Ingenierías y Humanidades	317	Acción
		Infraestructura para la Mejora Educativa			
			Mejora Continua de la Infraestructura Educativa	311	Programa
			Infraestructura e Impulso Artístico y Deportivo en las Escuelas	318	Proyecto
		Ampliación de la Oferta Educativa			
		Fortalecimiento del Sistema Educativo			
			Convenios de Vinculación Escuela-Empresas	312	Acción
			Transformando Sonora Escuela-Empresas	251	Acción
			Nivelación y Reincorporación Escolar	308	Acción
			Reconstrucción de la Confianza Gobierno-Estudiantes	316	Acción
			Retiro Digno a Maestros	304	Acción
			Transparencia en la Asignación de Plazas Docentes	306	Acción
			Condiciones de Trabajo Digno a los Maestros	296	Acción
			Aprovechamiento de la Infraestructura Escolar en Turnos Vespertino	291	Acción
		Impulso a la Creación y Manifestación Cultural			
			Incremento de la Oferta de Proyectos y Actividades Culturales e Históricas de Empalme	277	Acción
			Fomento del Arte, la Cultura y el Deporte	240	Acción
			Cultura Económica y Creativa	12	
			Desarrollo Cultural Plural y Diverso	284	Acción
			Promoción de Cooperativas Creativas de Creadores Locales	297	Acción
		Lectura para la Transformación			
			Edición de Todos los Clásicos	247	Acción
			Fomento a la Lectura y Apoyo a Creadores y Artistas Sonorenses	262	Acción
		Difusión Cultural			
			Preservación de Lugares y Zonas Arqueológicas	283	Acción
			Sonora Destino de la Industria Fílmica	158	Proyecto
			Impulso a las Contiendas de Jaripeos	248	Acción
			Promoción de Artesanías Locales y Regionales	108	Acción
		Impulso al Deporte			
			Creación de Tres Centros Deportivos de Alto Rendimiento	229	Acción
			Promoción de la Liga Regional de Béisbol	215	Acción
			Competencias Deportivas Interescolares	232	Programa
			Competencias Interculturales	214	
			Competencias Deportivas Estatales	231	

			Competencias Internacionales	236	
		Jóvenes para la Transformación			
			Observatorio Juvenil	42	Proyecto
			Gabinete Integrado por Jóvenes	8	Acción
			Formación de Jóvenes Talentos	282	Acción
			Creación de Espacios de Creación y Recreación Juvenil	315	Acción
			Combate a Desigualdad	72	Acción
		Inclusión y Transformación Tecnológica			
			Canasta Tecnológica para la Educación y la Conectividad	263	Acción
	Fortalecimiento de las Instituciones Municipales				
		Fortalecimiento Municipal			
			Respeto a la Autonomía Municipal	11	Acción
			Impulso a la Competitividad Municipal	40	Acción
	Buen Gobierno para la Regeneración Democrática.				

Eje	Objetivo	Tema	Compromiso/Subtema	N° Compromiso	Tipo Compromiso
		Gobierno Transparente (No Mentir)			
			Transformación Digital del Gobierno	15	Acción
			Transparencia en el Acceso a la Información	205	Acción
			Contraloría Social Ciudadana para las Subastas y Contrataciones	61	Acción
			Digitalización en el Gobierno	58	Acción
			Licitaciones Transparentes	52	Acción
			Tecnología para la Resolución de Problemas Sociales	217	Acción
			Mejora Regulatoria de la Inversión	100	Acción
			Portal Universal para Trámites	56	Acción
			Gobierno Digital, Eficiente y Transparente	22	Acción
			3 de 3 a Todos los Servidores Públicos	23	Acción
			Gobierno Transparente (No Mentir)	30	
			Impulso a un Auténtico Servicio Civil de Carrera	57	Acción
		Gobierno Eficiente (No Robar)			
			Desarticulación de la Red de Complicidades	9	Acción
			Gobierno Eficiente (No Robar)	50	Acción
			Poder Judicial Justo y Eficaz	200	Acción
			Combate a Fondo de la Corrupción	4	Acción
			Eficiencia del Sistema Estatal Anticorrupción	51	Acción
			Catálogo de Precios y Contratos para las Dependencias	53	Acción
			Uso Racional y Transparente del Gasto	307	Acción
			Inversión Imprescindible	15	
			Jóvenes para la Transformación	1	
			Política de Responsabilidad Histórica y Social	55	Acción
			Control de Confianza a Funcionarios	202	Acción
			Trámites sin Sobornos ni Extorsión	206	Acción
			Eficiencia Administrativa y de Gestión Gubernamental	24	Acción
			Congreso con Gasto Mínimo	27	Acción
			Procesos de Compras Públicas, Licitación y Obras Competitivas y Ab	60	Acción
			Certificación y Depuración de los Cuerpos de Seguridad	66	Proyecto
			Combatir la Corrupción en los Cuerpos de Seguridad	67	Acción
			Agilización de Procesos de Denuncias	187	Programa
			Mejora del Sistema de Declaración Patrimonial	204	Acción
			Gobierno Austero y Eficaz	10	Acción
			Gobierno con Costo Mínimo	32	Acción
			Policía con Sensibilidad Social	147	
			Eliminar la Corrupción de las Juntas de Conciliación y Arbitraje	46	Acción
			Condiciones de Trabajo Digno a Trabajadores del Estado	43	Acción
			Instituciones Educativas Democráticas y sin Corrupción	321	Acción
			Combate a Fondo de la Corrupción en la Administración Pública	62	Acción
		Gobierno Democrático (No Traicionar)			
			Gobierno Democrático (No Traicionar)	28	
			Gobernar con el Ejemplo	59	
			Filantropía Social en el Estado	299	Programa

			Prioridades Presupuestarias	5	Acción
			Decreto Gubernamental para la Transformación (No Robar, No Mentir y no traicionar)	2	Acción
			El Mayor Gasto Social de la Historia de Sonora	207	
			Bienestar para la Primera Infancia	237	
			Fortalecimiento de las Instituciones de Justicia	118	Acción
			Democratización de la UGRS	41	Acción
El presupuesto social más grande de la historia					
	Política Social y Solidaria para el Bienestar				
		Bienestar Social			
			Apoyo a Familias Vulnerables	17	
			Pensión Universal Complementaria	235	Acción
			Red de Seguridad Social para el Bienestar	209	Acción
			Sonora Digna y Próspera	21	Programa
			Presupuesto Socialmente Redistributivo	26	Acción
			Albergues a Personas en Situación de Calle	222	Acción
			Espacios de Trabajo a Personas con Discapacidad	288	Acción
		Seguridad de los Migrantes			
		Dignidad a los Pueblos Originales.			
			Bienestar de las Etnias de Sonora		Acción
			Atención Especial a los Pueblos Indígenas	219	Acción

Eje	Objetivo	Tema	Compromiso/Subtema	N° Compromiso	Tipo Compromiso
		Vivienda para el Bienestar			
			Precio de Energía Eléctrica Asequible	33	Acción
			Vivienda Digna, Asequible y de Calidad	234	Proyecto
			Incentivos a Empresas Constructoras de Vivienda Accesible		Acción
		Transformación Urbana para el Bienestar			
			Sonora sin Pobreza Extrema	1	
			Equipamiento Urbano en Zonas Populares		Acción
			Adopción de Mascotas	218	Acción
			Veterinarias Públicas	211	Proyecto
			Colonias Dignas	78	Acción
			Creación de un Consejo para el Desarrollo Urbano	90	Acción
			Regularizaremos los Asentamientos Humanos Irregulares y Combatiremos rezago habitacional	228	Acción
			Rescate de Espacios Públicos para la Convivencia y el Esparcimiento	216	Acción
			Crearemos Espacios Públicos que Mejoren las Condiciones de Vida de los sonorenses	220	Acción
			Creación de Parques Lineales y de Bolsillo en Todo el Estado	95	Acción
			Ciudades Protegidas	14	Proyecto
			Rescataremos las Colonias, los Barrios y las Comunidades	15	
	Salud Universal				
		Salud Incluyente			
			Salud Universal	7	
			Cartillas de Salud para Personas con Síndrome de Down	287	Acción
			La Salud es la Prioridad	238	Acción
			Lucha Nacional contra la Obesidad	243	Acción
			Consumo Sano en Escuelas	243	Acción
			Protocolos para la Salud Sin Discriminación		Acción
		Salud de Calidad			
			Recuperación de Centros de Salud	293	
			Rescate del ISSSTESON	250	Acción
			Reconstrucción del Sistema de Salud	255	Programa
			Bases para el Personal de Salud	258	Acción
			Eficiencia en Tiempos para Citas y Atención Médica	292	Programa
			Recuperación de la Infraestructura Sanitaria	239	Acción
			Seguridad para el Personal Médico	259	Programa
			Seguimiento a la Estrategia Nacional de Prevención a las Adicciones	84	Acción

			Ampliación de Instituciones de Salud	245	
			Fortalecer Equipo Hospitalario	256	Acción
LA igualdad efectiva de derechos para todas y todos					
	Igualdad de derechos y equidad de género				
		Fortalecimiento y Equidad de Género			
			Agenda Ciudadana que Represente la Visión de las Mujeres	13	Programa
			Alerta Rosa	124	Acción
			Créditos Especiales a Mujeres para el Autoempleo	141	Acción
			Políticas Públicas Creadas por Mujeres	242	Acción
			Apoyos Económicos a Mujeres de Escasos Recursos	271	Programa
			Combate a la Violencia de Género	196	Programa
			Empoderamiento de la Mujer	4	
			Inclusión Social	11	
			Políticas para la Mujer y Contra la Violencia de Género	252	Programa
			Proyectos Productivos e Independencia Económica de la Mujer	265	Programa
			Estancias Infantiles	9	
			Un Gabinete con Equidad	241	
			Gobierno con Equidad de Género y sin Discriminación		Programa
			Capacitación en Perspectiva de Género	273	Acción
			Protocolos para Prevenir, Atender y Sancionar la Violencia Contra la mujer	253	Acción
			3 de 3 en Violencia de Género	268	Acción
			Presupuesto, Facultades y Certeza Jurídica al Instituto Sonorense de	269	Acción
			Combate a la Cultura del Machismo y el Sexismo	300	Acción
			Atención Especial a Feminicidios	274	Acción
			Atención Especial a Feminicidios	123	Acción
			Combatiremos la Discriminación Laboral y el Acoso	272	Acción
		Derechos de las Minorías			
			Derechos de las Minorías y de las Personas con Discapacidad	254	Acción
			Políticas Públicas para el Derecho a la Salud, la Educación y el Trabajo a las Personas LGBTTTI		Acción
			Prohibir las Terapias de Conversión		Acción
			Promover la Educación Integral en Sexualidad		Acción
			Combate a los Crímenes de Odio Contra las Personas LGBTTTIQ+		Programa

Eje	Objetivo	Tema	Compromiso/Subtema	N° Compromiso	Tipo Compromiso
			Matrimonio Igualitario		Acción
			Ampliar y Garantizar los Derechos de las Personas	246	Acción
			Inserción Social de Infractores Recurrentes	186	Acción
		Democracia Laboral			
			Respeto a los Derechos para Trabajadores	303	Acción
			Fortaleceremos la Negociación de Contratos Colectivos	295	Acción
			Democracia Sindical	47	Acción
	Sostenibilidad del Desarrollo Regional				
		Desarrollo Económico Inclusivo			
			Desburocratización para la Creación de Empresas	37	Acción
			Desburocratización para la Creación de Empresas	39	
			Facilitar la Inversión	69 6	Acción
			Prioridad a los Microempresarios, Transición Digital y Mejora Regulatoria	94	Acción
			Fortalecimiento del Autoempleo	164	Programa
			Vincular Academia y Empresas	163	Acción
			Impulso a la Economía Familiar	127	
			Relanzamiento y Rescate de Centros Turísticos	129	Acción
			Impulso al Programa de Promoción Turística Regional		Acción
			Desarrollo Armónico entre las Regiones Basado en los Principios de	98	Acción
			Reactivación Económica	14	

			Crecimiento Económico Parejo	89	Acción
			Promoción Turística de los Municipios		Acción
			Apoyo a las Micro, Pequeñas y Grandes Empresas de Turismo	128	Acción
			Acompañamiento Empresarial	122	Acción
		Desarrollo Económico Sostenido			
			Dar Más Valor Agregado al Cobre	170	Acción
			Impulso en Agroindustria	135	Acción
			Apoyo a Pescadores	151	Proyecto
			Valor Agregado a la Producción Local	112	Programa
			Cultura del Emprendimiento	161	Acción
			Generación de los Eslabones Necesarios en las Cadenas de Valor	162	Acción
			Ecosistema de Empresas Sociales y Cooperativas	3	Acción
			Integración de Cadenas Productivas	120	Proyecto
			Valor Agregado a la Producción Pecuaria	185	Proyecto
			Desarrollo del Turismo a Través de las Playas y Puertos Pesqueros	166	Acción
			Aprovechamiento de Potencialidades y Fortalezas Geográficas	210	Acción
		Desarrollo Económico Sostenible			
			Nueva Cultura Empresarial con Responsabilidad Social	88	Acción
			Manejo Consciente del Medio Ambiente Urbano	136	Acción
			Infraestructura para Generar Energías Renovables	144	Acción
			Economía más Amigable al Medio Ambiente	194	Acción
			Paneles Solares en Viviendas y Comunidades Aisladas	213	Proyecto
			Uso Racional del Agua y Recuperación de Residuos	195	Acción
			Cultura del Agua	192	Programa
			Realizaremos una Adecuada Gestión de Residuos	86	Acción
			Incentivar e Impulsar Inversión de la Industria Innovadora y Sustentables	76	Acción
			Política de Sustentabilidad del Desarrollo para Generar Energías Limpias y renovables	121	Acción
Coordinación histórica entre desarrollo y seguridad					
	Seguridad y Desarrollo				
		Seguridad para Sonora			
			Nueva Política de Seguridad	2	
			Crear la UIF	116	Acción
			Crear la Ley Antilavado	201	Acción
			Cero Defraudación Fiscal	203	Acción
			Coordinación Institucional para Garantizar Paz y Tranquilidad	63	Acción
			Prestaciones Justas y Salario Digno para Policías	64	Acción
			Implementación de un Plan de Vida y Carrera Policial	65	Acción
			Preparación, Capacitación y Entrenamiento de Elementos de Seguridad	68	Acción
			Regresar la Paz a Magdalena, Caborca, Guaymas, Cajeme y Nogales	74	Acción
			Exámenes de Confianza y Antidoping	111	Programa
			Agencia de Inteligencia Estatal	198	Acción
			Consolidación de la Unidad de Análisis Criminal de Vanguardia	199	Proyecto
			Orden, Control y Disciplina en los Cuerpos de Seguridad	80	Acción
			Combate a las Causas que Generan la Violencia	82	Acción
			Presupuesto para el Sistema de Procuración de Justicia	85	Acción
			Instituciones para la Seguridad	75	Acción

Eje	Objetivo	Tema	Compromiso/Subtema	N° Compromiso	Tipo Compromiso
			Mando Policial Coordinado	115	Acción
			Reclutamiento en la Policía	79	
			Academia Estatal para Policías	83	
			Coordinación Directa del Gabinete de Desarrollo con Seguridad	125	Acción
			Fortalecimiento del C5	197	Acción
		Transformación Institucional para la Seguridad de los Trabajadores			

			Reforma Laboral	45	
			Implementación de la Reforma Laboral	48	
			Mejorar Condiciones de Trabajo	208	
			Reforma Laboral	49	
			Atención a las Demandas Legítimas Sindicales	44	
	Reactivación del Crecimiento Económico con Finanzas Sanas				
		Finanzas Sanas para la Recuperación y la Transformación			
			Banco Estatal de Bienestar y Desarrollo	6	
			Equilibrio Fiscal sin Nuevos Impuestos ni Condonaciones	101	Acción
			Inversión sin Obstáculos	126	Acción
			Austeridad Republicana	3	Programa
			Sanidad Financiera	25	
			Finanzas Sanas y sin Corrupción	38	Acción
			Cancelación de Pensiones Casi Millonarias en el ISSSTESON	305	Acción
			Ahorrar para el Bienestar	12	Acción
			Finanzas Públicas en Equilibrio	20	Acción
			Habrá Disciplina Financiera	19	Acción
		Reactivación y Transformación Económica			
			Creación del Fondo de Bienestar	188	
			Recuperación y Preservación de Empleos	113	Acción
			Promoción de Ferias Ganaderas	107	Acción
			Premios para Productores Agrícolas y Ganaderos	109	Acción
			Mejorar el Arribo de los Turistas a Sonora		Acción
			Programa de Desarrollo para Generar más de 30 mil Empleos	149	Acción
			Litio como Polo de Desarrollo en Sonora	178	Acción
			Concursos de Caballos, Toros, Vacas Lecheras	110	Proyecto
			Apoyo a los Sectores de Minería, Campo, Pesca	138	Acción
			Facilidades y Garantías a Extranjeros Interesados en Invertir en Son	70	Acción
	Infraestructura para el Desarrollo Económico Inclusivo				
		Movilidad Eficiente y Sustentable			
			Inversión Pública Histórica del 10% Anual	189	Acción
			Mejora y Eficiencia del Sistema de Transporte Público Masivo	92	
			Mejora y Eficiencia del Sistema de Transporte Público Masivo para	93	Acción
			Rescate del Centro de Hermosillo	91	Proyecto
			Infraestructura Social y Pública a las Comunidades Rurales y de Jornaleros migrantes	225	Acción
			Malecones e Infraestructura Urbana en San Carlos y Bahía de Kino	129	Acción
		Infraestructura para el Desarrollo			
			Infraestructura para el Desarrollo	31	Acción
			Construcción de Represos en Álamos	96	Acción
			Mejoramiento de la Red de Distribución de Agua	87	Acción
			Acceso Universal a los Servicios Públicos		Acción
			Plantas Tratadoras de Agua		Acción
			Represos para Proteger Comunidades en Situación de Riesgo		Proyecto
			Rescate y Conclusión de Obras Inconclusas	103	Acción
			Revestimiento de Canales de Riego	134	Proyecto
			Plantas Tratadoras de Agua	179	Acción
			Construcción de una Presa en Quiriego	183	Proyecto
			Infraestructura que requiere Empalme en Materia de Protección Civil	154	Acción
			Pozos de Agua con Energía Solar en Comunidades sin Electricidad	233	Proyecto
			Rescatar el Centro Histórico de Nogales	173	Proyecto
			Balance Hídrico en el Acuífero y Modernización del Sistema de Riego	191	Proyecto
		Infraestructura para la Articulación y Conexión con el Mercado Global			
			Revitalizaremos los Parques Industriales	140	Acción

Fuente: Cuadro proporcionado por la Coordinación de Planeación y Comisiones del Consejo Consultivo para el Plan Estatal de Desarrollo 2021-2027.

XI. EVALUACIÓN Y SEGUIMIENTO DEL PLAN MUNICIPAL DE DESARROLLO

La importancia de evaluar radica en la necesidad de conocer el impacto y generar elementos de toma de decisiones debido a que la evaluación proporciona información que se ofrece al contribuyente, a los funcionarios del Ayuntamiento, al H. Congreso y población en general, además de que es elemento básico para la orientación de las políticas públicas, de igual forma da respuesta a las siguientes preguntas:

- ¿Qué impacto o resultado se ha obtenido en el bienestar de la población y en la gestión administrativa?
- ¿Es suficiente lo que se hizo, cubre los requerimientos de la población?
- ¿Qué tan bien o mal se hizo?
- ¿Qué se necesita hacer para mejorar los resultados hasta ahora obtenidos?

La evaluación por tanto permite valorar y calificar el desempeño de las diferentes dependencias y organismos que integran la administración pública municipal en términos de los resultados obtenidos y del cumplimiento de los objetivos.

La existencia de información cualitativa y cuantitativa soporta el proceso de elaboración del reporte de avance trimestral, del Informe de Gobierno, y la integración del Informe de Avance en la Ejecución del Plan Municipal de Desarrollo pero, sobre todo, da rumbo al planteamiento de políticas, nuevos objetivos o metas, atendiendo a que el entorno municipal es cambiante y por tanto los procesos de planeación deben ser dinámicos.

Finalmente, con la evaluación se cumple la normatividad que contempla su ejecución como una obligación del Gobierno Municipal.

Enfoque de la Evaluación

Se propone que la evaluación del Plan Municipal de Desarrollo, así como de los programas que de éste se derivan, se realice bajo dos grandes enfoques:

1. Evaluación Estratégica (evaluación de logros e identificación de resultados.)
2. Evaluación programática-presupuestal (avance de acciones relevantes).

La evaluación estratégica estará orientada a identificar el nivel de cumplimiento de los objetivos y las metas globales establecidas (logros, productos e impacto de las acciones) por cada uno de los programas y proyectos establecidos en el programa anual y que surgen del Plan Municipal de Desarrollo y de esta forma medir el desempeño de las dependencias que integran la administración pública de cada municipio.

Esta actividad se desarrolla de manera trimestral, mediante la implementación de indicadores de evaluación del desempeño y con la operación de un Sistema de Evaluación al Desempeño.

Por su parte, la evaluación programática-presupuestal estará referida a valorar el alcance de los objetivos, metas, obras y acciones establecidos en el Programa Operativo Anual, para mostrar el aprovechamiento, transparencia y eficiencia del uso de los recursos públicos, utilizando el método del presupuesto basado en resultados y deberá ser evaluado por periodos trimestrales.

La aplicación de este enfoque se llevará a cabo mediante el seguimiento y control de la ejecución de los proyectos, obras y acciones contemplados en los Programas Operativos Anuales (PBR), bajo el esquema de presupuesto por programas que actualmente ya utilizan los Ayuntamientos de la entidad.

Planeación

El impacto del Sistema en la etapa de planeación se refleja en una mejor sincronización entre el diseño de los programas con los planes y las demandas de los beneficiarios. Lo anterior se logra mediante el procedimiento de determinación de indicadores del desempeño.

Programación

En la etapa de programación, el sistema contribuye a comparar la efectividad del gasto en programas, mediante el uso de indicadores de costo-efectividad.

El acceso a los indicadores de costo-efectividad se irá generalizando de manera gradual, con el propósito de familiarizar al personal de las dependencias y organismos municipales relacionados con la administración del gasto con su aplicación práctica.

Presupuestación

En lo que respecta a la etapa de presupuestación, el sistema propiciará una asignación del gasto más objetiva y racional. Ello se logra al subordinar dicho proceso al logro de metas de desempeño y análisis de costo-efectividad.

En este sentido, el sistema permitirá un avance significativo respecto al proceso tradicional de asignación del gasto, basado en niveles históricos de recursos asignados más actualizaciones por inflación y consideraciones macroeconómicas.

Operación

En la etapa de operación, el sistema contribuirá a ser flexible la operatividad de los programas y a fomentar el cambio de la cultura hacia resultados, la satisfacción de beneficiarios y la evaluación de costos. Esto se logrará al incluir un acuerdo de flexibilización y mayor autonomía operativa de los programas como parte de los convenios o acuerdos de desempeño y al utilizar indicadores como parámetros básicos de evaluación de los mismos.

Control

El sistema representará un cambio de fondo en la función del control donde el contralor interno deberá incorporar incentivos o sanciones con base en auditorias por los resultados alcanzados.

Lo anterior permitirá recompensar —mediante reconocimientos al desempeño— a aquellas áreas/programas/funcionarios/ que obtengan los mejores resultados en la administración de programas y observar a quienes no cumplan con las metas de desempeño establecidas.

Evaluación

Finalmente, bajo esta nueva perspectiva, el enfoque de evaluación cambia de volúmenes de actividad a resultados alcanzados en diferentes dimensiones impacto, cobertura, eficiencia y calidad.

Lo anterior implicará la necesidad de contar con nuevas variables de información, tales como costos unitarios o niveles de satisfacción de los beneficiarios.

XII. MATRICES DE INDICADORES DE RESULTADOS

EJE RECTOR	GOBIERNO EFICIENTE Y HONESTO					
Objetivo 1.1.	RESUMEN NARRATIVO	INDICADORES	Método de cálculo	MEDIOS DE VERIFICACIÓN	FRECUENCIA	SUPUESTOS
FIN	Contribuir a ala eficiencia y eficacia en el manejo de la Hacienda Pública Municipal	Cobertura precupuestal en la implementación del PBR-SED	(monto de presupuesto de egresos operado bajo el esquema de PBR-SED / monto total del prepuesto de egresos) * 100	Informe de cierre del ejercicio fiscal del año que corresponda e informes de evaluación anual de los programas presupuestarios.	Anual	Existen las condiciones políticas, administrativas y presupuestales para soportar el proceso de implementación y consolidación del pbr-sed y la armonización contable
PROPÓSITO	Mantener una estructura contable armonizada	Porcentaje de programas presupuestarios operados bajo el esquema PBR-SED	(Programas operados con esquema PBR-SED / Total de programas presupuestarios operados en el año) * 100	Presupuesdo de Egresos aprobado por el Ayuntamiento / Calificación anual de la SHCP referenta al avance en la implementación del PBR-SED	Anual	Existen las condiciones políticas, administrativas y presupuestales para soportar el proceso de implementación y consolidación del pbr-sed
COMPONENTE 1	Las finanzas públicas fortalecidas a través de los ingresos del municipio	Porcentaje de cumplimiento del presupuesto de ingresos propios autorizado	(ingresos propios recaudados / ingresos propios presupuestados) * 100	Comparativo de ingresos de la Cuenta Pública	Semestral	Los contribuyentes acuden a realizar el pago de sus obligaciones fiscales municipales
ACTIVIDADES 1	Acciones para incrementar los ingresos propios por concepto de impuestos, derechos, licencias, productos, contribuciones por mejoras y aprovechamientos	Porcentaje de acciones realizadas para incrementar los ingresos propios	(Acciones realizadas / acciones programadas) * 100	Programa de trabajo de la Tesorería Municipal / Área de Ingresos	Trimestral	Se implementan mecanismos para facilitarle al contribuyente el pago de sus obligaciones fiscales
Actividad 2	El gasto se prioriza y se optimiza a través de la utilización e implementación de herramientas de planeación y presupuestación estratégicas	Porcentaje de programas presupuestarios con MIR respecto al total de los programas presupuestarios	(Programas presupuestarios que cuentan con MIR / Total de programas presupuestarios) * 100	Presupuesto de Egresos autorizado para el Ejercicio Fiscal 2022 / Programa Anual de Evaluación de los programas presupuestarios.	Semestral	Existe interés de las dependencias y entidades para participar en la integración de un presupuesto basado en resultados
ACTIVIDAD 2.1	Programas presupuestarios rediseñados y aliniados con el Plan Municipal de Desarrollo	Procentaje de los temas prioritarios del PMD cubiertos con los programas sujetos a evaluación	(Temas prioritarios del Plan Municipal de Desarrollo /Programas presupuestarios sujetos a evaluación) * 100	Matriz de alineación de los programas presupuestarios con el Plan Municipal de Desarrollo	Trimestral	Las dependencias y entidades participan en su elaboración y avalan el catálogo de programas prespuestarios para resultados
ACTIVIDAD 2.2	Los programas presupuestarios se evalúan	Procentaje de evaluación de los programas presupuestarios	(Total de programas prespuestarios sujetos a evaluación / Total de programas presupuestarios evaluados) * 100	Programa Anual de Evaluación	Trimestral	El ayuntamiento cuenta con una unidad de evaluación al desempeño
COMPONENTE 3	Contabilidad Gubernamental Armonizada	Porcentaje de cumplimiento de la Ley General de Contabilidad Gubernamental.	(Número de lineamientos de la Ley General de Contabilidad Gubernamental cumplidos / Total de lineamientos que correspondan al área de Tesorería) * 100	Resultados de evaluación, reportes y auditoría por parte de CONAC-ISAF-ASF	Trimestral	Existe buena disposición de las autoridades hacendarias del municipio, así como importante nivel de coordinación con las dependencias y entidades, y resursos prespuestales y humanos para llevar a cabo la tarea
ACTIVIDAD 3	Sistema de contabilidad del municipio de acuerdo a lo establecido en la Ley General de Contabilidad Gubernamental armonizado	Porcentaje de actualización de software por la Contabilidad Gubernamental	(Disposiciones de la Ley General de Contabilidad Gubernamental integradas al software / Total de disposiciones de LGCG) * 100	Resultados de evaluación, reportes y auditoría por parte de CONAC-ISAF-ASF	Semestral	Existe buena disposición de las autoridades hacendarias del municipio, así como importante nivel de coordinación con las dependencias y entidades, y resursos prespuestales y humanos para llevar a cabo la tarea

EJE RECTOR 1	GOBIERNO EFICIENTE Y HONESTO					
Objetivo 1.2.	RESUMEN NARRATIVO	INDICADORES	Método de cálculo	MEDIOS DE VERIFICACIÓN	FRECUENCIA	SUPUESTOS
FIN	Combatir la corrupción mediante la promoción de la transparencia y una actitud servicial hacia los ciudadanos.	Variación anual de las observaciones a la cuenta pública	(Observaciones de la cuenta pública del año actual / observaciones de cuenta pública del año anterior) * 100	Resultado de la revisión de la Cuenta Pública por ISAF. Informes de auditoría por despachos externos	Anual	Las instituciones municipales participan activamente en la solventación de observaciones.
PROPÓSITO	La gestión pública, la rendición de cuentas y la confianza ciudadana son fortalecidas	Porcentaje de observaciones solventadas por ISAF de informes preliminares	(Observaciones de la cuenta pública solventadas / Total de observaciones emitidas a la cuenta pública por ISAF) * 100	Informes preliminares de ISAF	Anual	Las instituciones municipales participan activamente en la solventación de observaciones.
COMPONENTE 1	Instituciones con controles internos fortalecidos y operando	Porcentaje de observaciones internas solventadas	(Observaciones internas solventadas / Total de observaciones internas emitidas por OCEG) * 100	Informes de auditoría del órgano de control y evlauación gubernamental	Semestral	Las instituciones municipales participan activamente en la solventación de observaciones.
ACTIVIDADES 1	Instituciones municipales auditadas	Porcentaj de auditorías realizadas	(Auditorías a dependencias y entidades realizadas / Auditorías de dependencias y entidades programadas) * 100	Programa de Auditoría Gubernamental de Auditoría del Órgano de Control y Evaluación Gubernamental	Trimestral	Las instituciones municipales coadyuvan con el OCEG para el debido cumplimiento del programa.
COMPONENTE 2	Se aplican sanciones administrativas	Porcentaje de sanciones aplicadas	(Sanciones administrativas aplicadas contra servidores públicos / Total de quejas y denuncias recibidas contra servidores públicos) * 100	Informes mensuales y trimestrales de actividades del OCEG	Semestral	Las instituciones municipales, los servidores públicos y la ciudadanía cooperan denunciando todo presunto acto de corrupción.
ACTIVIDAD 2.1	Evolución del patrimonio de los servidores públicos vigilado	Porcentaje de verificación de la información contenida en las Declaraciones de Situación Patrimonial	(Verificaciones de la información contenida en las DSP / Verificaciones de información contenida en las DSP programadas) * 100	Programa de situación patrimonial de los servidores públicos	Trimestral	Los servidores públicos obligados del municipio cumplen con la obligación de presentar la Declaración de Situación Patrimonial
COMPONENTE 3	Desarrollo administrativo para fortalecer las capacidads institucionales	Porcentaje de atención a disposiciones administrativas	(Disposiciones administrativas de las dependencias y entidades atendidas / Total de disposiciones administrativas de las dependencias y entidades que requieren atención) * 100	Informe mensual y trimestral de actividades del OCEG	Trimestral	Los servidores públicos y las instituciones cooperan con OCEG para la atención de disposiciones administrativas
ACTIVIDAD 3.1	Actualizar los manuales de Organización y de Procedimientos de las dependencias y entidades de la Administración Pública Municipal	Porcentaje de atención al programa de actualización de los manuales de organización y procedimientos	(Manuales de organización o procedimientos actualizados / Manuales de organización o procedimientos programados para actualizar) * 100	Informe mensual y trimestral de actividades del OCEG	Semestral	Los servidores públicos y las instituciones cooperan con OCEG para la actualización de manuales de organización y procedimientos
ACTIVIDAD 3.2	Atender en tiempo y forma todas las solicitudes de información presentadas por la ciudadanía al Ayuntamiento.	Porcentaje de atención a disposiciones administrativas	(Disposiciones administrativas de las dependencias y entidades atendidas / Total de disposiciones administrativas de las dependencias y entidades que requieren atención) * 100	Informe mensual y trimestral de actividades del OCEG	Semestral	Los servidores públicos y las instituciones cooperan con OCEG para la atención de disposiciones administrativas
ACITIVIDAD 3.3	Visitas periódicas del alcalde a los distintos barrios del municipio	Alcanzar por lo menos una visita a cada barrio en el total del trienio	Registro de visitas	Informe mensual y trimestral de actividades del OCEG	Trimestral	Los servidores públicos y las instituciones cooperan con OCEG para la atención de disposiciones administrativas

EJE RECTOR	GOBIERNO EFICIENTE Y HONESTO					
Objetivo 1.3.	RESUMEN NARRATIVO	INDICADORES	Método de cálculo	MEDIOS DE VERIFICACIÓN	FRECUENCIA	SUPUESTOS
FIN	Promover el saneamiento de las finanzas municipales sanas	((Ingresos propios reales recaudados por el municipio en el año evaluado - Ingresos propios reales recaudados por el municipio en el año previo al evaluado) / Ingresos propios reales recaudados por el municipio en el año previo al evaluado) * 100	Tasa de crecimiento real anual de los ingresos propios	Comparativo de ingresos de la Cuenta Pública	Anual	Los contribuyentes acuden a realizar el pago de sus obligaciones fiscales municipales
PROPÓSITO	La recaudación local crece	Ingresos propios reales recaudados por el municipio en el año evaluado - Ingresos propios reales recaudados por el municipio en el año previo al evaluado	Diferencia de ingresos propios del año evaluado con respecto al anterior	Comparativo de ingresos de la Cuenta Pública	Anual	Los contribuyentes acuden a realizar el pago de sus obligaciones fiscales municipales
COMPONENTE 1	Crecimiento real anual de la recaudación por derecho de agua	((Monto real del derecho de agua recaudado por el municipio en el año evaluado - Monto real del derecho de agua recaudado por el municipio en el año previo al evlauado) / Monto real del derecho de agua recaudado por el municipio en el año previo al evaluado) * 100	Tasa de crecimiento real anual de la recaudación por derecho de agua	Comparativo de ingresos de la Cuenta Pública	Anual	Los consumidores del servicio pagan a tiempo la tarifa del servicio de agua
ACTIVIDADES 1.1	Regularizar tomas de agua con base en las subdivisiones de vivienda	Viviendas particulares habitadas - Cantidad de tomas de agua	Diferencia entre viviendas particulares habitadas y tomas de agua existentes	Censo de Población y Vivienda 2020, INEGI y registro de tomas de agua	Anual	Las subdivisiones de vivienda son irregulares y sólo se considera una toma para varias
ACTIVIDADES 1.2	Actualización anual de la tarifa de agua con base en el INPC	(Tarifa por derecho de agua vigente * Porcentaje de variación según INPC) + Tarifa por derecho de agua vigente	Actualización de la nueva tarifa por derechos de agua según INPC	Índice Nacional de Precios al Consumidor del INEGI y tarifa de agua vigente	Anual	El mantenimiento de una tarifa fija por derechos de agua
ACTIVIDADES 1.3	Crear tarifas diferenciadas basadas en los usos de suelo aplicados					
COMPONENTE 2	Regularizar el cobro del predial urbano y rural	((Monto real recaudado por impuesto predial en el año evaluado - Monto real recaudado por impuesto predial en el año previo al evaluado) / Monto real recaudado por impuesto predial en el año previo al evaluado) * 100	Tasa de crecimiento real anual de la recaudación por impuesto predial	Comparativo de ingresos de la Cuenta Pública	Anual	Los contribuyentes acuden a realizar el pago de sus obligaciones fiscales municipales
ACTIVIDAD 2.1	Contar con una tabla actualizada de zonificación de uso de suelo y valores catastrales	Tabla actualizada de zonificación de uso de suelo y valores catastrales	Plano de usos de suelo y valores catastrales	ICRESON y Programa Municipal de Desarrollo Urbano	Anual	El ICRESON mantiene el convenio para actualizar los valores catastrales
ACTIVIDAD 2.2	Llevar a cabo un proceso de inspección del cumplimiento de los usos de suelo	Inspección de usos de suelo acorde a lo expedido por el Ayuntamiento y expuesto en el Programa Municipal de Desarrollo Urbano	Dictamen y plano de uso de suelo	Programa Municipal de Desarrollo Urbano	Anual	Los solicitantes cumplen con el uso de suelo aprobado por el Ayuntamiento
ACTIVIDAD 2.3	Crear un apartado de sanciones por el incumplimiento de los usos de suelo	Apartado de sanciones por incumplimiento de los usos de suelo en Ley de Ingresos de año entrante	Apartado de desarrollo urbano en Ley de Ingresos Municipal	Ley de Ingresos del municipio	Anual	El congreso aprueba la modificación a la Ley de Ingresos Municipal
ACTIVIDAD 2.4	Gestionar convenio con el estado para el cobro del impuesto predial	Oficio de convenio con gobierno del estado	Contar con oficio	Minuta de reunión, oficio a cargo de tesorería	Anual	El gobierno del estado, por medio de ICRESON, facilita y actualiza la información catastral

EJE RECTOR 2	BIENESTAR SOCIAL					
Objetivo 2.1.	RESUMEN NARRATIVO	INDICADORES	MÉTODO DE CÁLCULO	MEDIOS DE VERIFICACIÓN	FRECUENCIA	SUPUESTOS
FIN	Garantizar el acceso a suelo y vivienda de todos los pobladores del municipio	Déficit de vivienda	Hogares existentes - viviendas existentes	Censos de población y vivienda, INEGI	Quinquenal	Existe demandantes de suelo y vivienda
PROPÓSITO	La población del municipio cuenta con una vivienda					
COMPONENTE 1	Crear reservas territoriales municipales para la construcción de vivienda de interés social y popular	Tasa de crecimiento en hectáreas de la reserva territorial municipal	((Hectáreas de reserva territorial municipal en el año evaluado - hectáreas de reserva territorial municipal en el año previo al evaluado) / hectáreas de reserva territorial municipal en el año previo al evaluado) * 100	Sindicatura	Anual	Existe una necesidad de suelo urbano para la construcción de vivienda popular.
ACTIVIDADES 1	Cuantificar la demanda y definir las condiciones socioeconómicas para el otorgamiento de suelo urbano	Crear términos de referencia para el otorgamiento de suelo urbano a quien lo necesite	Contar con documento	Sindicatura	Semestral	Existe una necesidad de suelo urbano para la construcción de vivienda popular.
ACTIVIDADES 1.2	Definir espacios susceptibles al aprovechamiento urbano	Validación técnica	Contar con un documento que valide tecnicamente la ocupación ordenada del suelo	Documento	Semestral	Existe una necesidad de suelo urbano para la construcción de vivienda popular.
ACTIVIDADES 1.3	Crear un programa de reocupación de vivienda abandonada	Tasa de crecimiento de vivienda abandonada	((Número de viviendas abandonadas en el año evaluado-Número de viviendas abandonadas en el año previo al evaluado) / Número de viviendas abandonadas en el año previo al evaluado) * 100	Censos propios, registro al programa	Semestral	Existe una necesidad de suelo urbano para la construcción de vivienda popular.
COMPONENTE 2	Elaborar un programa municipal de desarrollo urbano y/o de ordenamiento ecológico territorial que defina los espacios susceptibles al crecimiento, mejoramiento y consolidación urbana, así como los espacios destinados a la protección y restauración ambiental y aprovechamiento productivo.	Publicación del Programa Municipal de Desarrollo Urbano o del Programa de Ordenamiento Ecológico Municipal	Registro de publicación	Boletín Oficial del Estado de Sonora	Anual	Existen inversiones con importantes impactos sociales, económicos y ambientales que suponen su regulación desde el ámbito local.
ACTIVIDADES 2.1	Elaborar un instrumento de planeación territorial local que tenga como objetivo reglamentar los usos del suelo al interior del municipio	Publicación del Programa Municipal de Desarrollo Urbano o del Programa de Ordenamiento Ecológico Municipal	Registro de publicación	Boletín Oficial del Estado de Sonora	Anual	Existen inversiones con importantes impactos sociales, económicos y ambientales que suponen su regulación desde el ámbito local.

EJE RECTOR 2	BIENESTAR SOCIAL					
Objetivo 2.2.	RESUMEN NARRATIVO	INDICADORES	MÉTODO DE CÁLCULO	MEDIOS DE VERIFICACIÓN	FRECUENCIA	SUPUESTOS
FIN	Alcanzar un grado promedio de escolaridad superior a la media estatal	Grado promedio de escolaridad	Promedio de años estudiados	Censos de población y vivienda del INEGI	Quinquenal	Existe intención por los alumnos de menores recursos por continuar estudios.
PROPÓSITO	Los estudiantes continúan con sus estudios de nivel medio superior y superior	Porcentaje de la población en edad de estudiar que estudia	Población en edad de estudiar que estudia / Total de la población en edad de estudiar	Listas de alumnos y censos de población y vivienda, 2020	Anual	Existe intención por los alumnos de menores recursos por continuar estudios.
COMPONENTE 1	Evitar la deserción escolar	Porcentaje de alumnos que desertan	Total de alumnos inscritos - Total de alumnos graduados	Listas de alumnos por nivel escolar	Anual	Existe intención por los alumnos de menores recursos por continuar estudios.
ACTIVIDADES 1.1	Gestionar becas para alumnos que, por causas socioeconómicas, no pudieran permanecer en la escuela	Porcentaje de alumnos que solicitan becas	(Total de alumnos apoyados en integrar documentación para becas / Total de solicitudes de becas) * 100	Solicitudes de alumnos	Semestral	Existe intención por los alumnos de menores recursos por continuar estudios.
ACTIVIDADES 1.2	Campañas sobre sexualidad, adicciones y civismo	Actividades realizadas	Cantidad de actividades realizadas	Invitaciones, memorias fotográficas, archivo, convocatorias	Semestral	Existe disposición de las autoridades educativas y gubernamentales para llevar a cabo las actividades.
ACTIVIDADES 1.3	Atención psicológica a niños y jóvenes	Número de psicólogos por estudiantes del municipio	Número de estudiantes del municipio / cantidad de psicólogos	Nómina escolar	Semestral	Existe posibilidad de incluir psicológos dentro de la nómina escolar
ACTIVIDADES 1.4	Atención especial a niños y jóvenes	Número de maestros de educación especial por estudiantes del municipio. No superar 1 por cada 50 niños.	Número de estudiantes del municipio / cantidad de profesores de eduación especial	Nómina escolar	Semestral	Existe posibilidad de gestionar la presencia de un profesor de educación especial dentro de la nómina escolar
ACTIVIDAD 1.5	Dotar de internet gratuito a estudiantes que lo requieran	Porcentaje de estudiantes con internet gratuito	(Estudiantes con internet gratuito / Total de estudiantes) * 100	Programa Operativo Anual, Informe Anual	Semestral	La sociedad estudiantil y las autoridades educativas mantienen el interés en los proyectos educativos y culturales.
ACTIVIDAD 1.6	Dotar de útiles escolares a la población en nivel educativo básico	Porcentaje de estudiantes beneficiados	(Estudiantes beneficiados / total de estudiantes) * 100	Programa Operativo Anual, Informe Anual	Semestral	La sociedad estudiantil y las autoridades educativas mantienen el interés en los proyectos educativos y culturales.
ACTIVIDAD 1.7	Creación de un huerto comunitario o parcela escolar	Metros cuadrados de huerto comunitario o parcela escolar produciendo	Metros cuadrados de huerto comunitario o parcela escolar produciendo	Programa Operativo Anual, Informe Anual	Semestral	La sociedad estudiantil y las autoridades educativas mantienen el interés en los proyectos educativos y culturales.
COMPONENTE 2	Fomentar el ingreso de jóvenes a instituciones de educación superior	Porcentaje de alumnos inscritos	(Total de alumnos inscritos en educación superior en el año / total de alumnos egresados del nivel medio superior) * 100	SEP, investigación	Semestral	La sociedad estudiantil y las autoridades educativas mantienen el interés en los proyectos educativos y culturales.
ACTIVIDAD 2.1	Crear un padrón de estudiantes con necesidades de apoyo de manutención para proseguir sus estudios de nivel superior	Porcentaje de estudiantes con necesidades de apoyo de manutención	(Estudiantes de educación superior con apoyos de manutención otorgados / estudiantes de educación superior que enviaron solicitud para el apoyo en manutención) * 100	Solicitudes de alumnos	Semestral	La sociedad estudiantil y las autoridades educativas mantienen el interés en los proyectos educativos y culturales.
ACTIVIDAD 2.2	Gestionar recursos estatales, federales y/o privados para la creación de una casa del estudiante de San Felipe de Jesús	Oficio y acuse de recibido	Oficio y acuse de recibido	Oficio y acuse de recibido	Trimestral	La sociedad estudiantil y las autoridades educativas mantienen el interés en los proyectos educativos y culturales.
COMPONENTE 3	Difundier actividades culturales y deportivas que refuercen el interés educativo	Actividades realizadas	Cantidad de actividades realizadas	Invitaciones, memorias fotográficas, archivo, convocatorias	Semestral	Existe disposición de las autoridades educativas y gubernamentales para llevar a cabo las actividades.
ACTIVIDADES 3.1	Fomentar actividades culturales	Actividades realizadas	Cantidad de actividades realizadas	Invitaciones, memorias fotográficas, archivo, convocatorias	Semestral	Existe disposición de las autoridades educativas y gubernamentales para llevar a cabo las actividades.
ACTIVIDADES 3.2	Fomentar actividades deportivas	Actividades realizadas	Cantidad de actividades realizadas	Invitaciones, memorias fotográficas, archivo, convocatorias	Semestral	Existe disposición de las autoridades educativas y gubernamentales para llevar a cabo las actividades.
ACTIVIDADES 3.3	Rehabilitación de estadio de beisbol	Monto de la inversión realizada	Cifra del monto aplicado para cumplir la actividad	Cuenta pública	Anual	Existe disposición de las autoridades para llevar a cabo las actividades.
ACTIVIDADES 3.4	Rehabilitación del parque recreativo "El Jojobal"	Monto de la inversión realizada	Cifra del monto aplicado para cumplir la actividad	Cuenta pública	Anual	Existe disposición de las autoridades para llevar a cabo las actividades.
ACTIVIDADES 3.5	Acondicionamiento del gimnasio municipal	Monto de la inversión realizada	Cifra del monto aplicado para cumplir la actividad	Cuenta pública	Anual	Existe disposición de las autoridades para llevar a cabo las actividades.

EJE RECTOR 2	BIENESTAR SOCIAL					
Objetivo 2.3.	RESUMEN NARRATIVO	INDICADORES	MÉTODO DE CÁLCULO	MEDIOS DE VERIFICACIÓN	FRECUENCIA	SUPUESTOS
FIN	Reducir las carencias materiales de la población	Porcentaje de población apoyada	(Población apoyada / población con solicitudes de apoyo) * 100	Programas de apoyo, oficios para gestión de recursos, listas de asistencia a capacitaciones	Trimestral	Que existan programas y disposición de otros órdenes de gobierno.
PROPÓSITO	En San Felipe de Jesús no hay carencias materiales de vivienda	Porcentaje de población apoyada	(Población apoyada / población con solicitudes de apoyo) * 100	Programas de apoyo, oficios para gestión de recursos, listas de asistencia a capacitaciones	Semestral	Que existan programas y disposición de otros órdenes de gobierno.
COMPONENTE 1	Promover y gestionar apoyos en especie y capacitación de trabajo a la población más vulnerable	Porcentaje de población apoyada	(Población apoyada / población con solicitudes de apoyo) * 100	Programas de apoyo, oficios para gestión de recursos, listas de asistencia a capacitaciones	Semestral	Que existan programas y disposición de otros órdenes de gobierno.
ACTIVIDADES 1.1	Implementar el programa "Rondas del Bienestar"	Porcentaje de población apoyada por el programa Rondas del Bienestar	(Población apoyada por el programa rondas del bienestar / población con solicitudes de apoyo del programa rondas de bienestar) * 100	Programas de apoyo, oficios para gestión de recursos, listas de asistencia a capacitaciones	Semestral	Que existan los recursos locales para crear los apoyos
ACTIVIDADES 1.2	Gestionar el acceso de la población a programas sociales del estado y la federación	Oficio y acuse de recibido	Oficio y acuse de recibido	Oficio y acuse de recibido	Trimestral	Que existan programas y disposición de otros órdenes de gobierno.
ACTIVIDADES 1.3	Crear convenios con el ICATSON para capacitación para el trabajo	Oficio de convenio firmado	Oficio de convenio firmado	Oficio de convenio firmado	Trimestral	Que exista disposición del ICATSON por llevar capacitaciones al municipio.
ACTIVIDADES 1.4	Facilitar el apoyo económico por parte de originarios del municipio en mejores condiciones socioeconómicas viviendo fuera del municipio	Porcentaje de donantes	(número de transacciones otorgados / número de personas inscritas como donantes) * 100	Estados de la cuenta en la que se concentran los apoyos	Trimestral	Que exista disposición de la gente que salió del municipio por apoyar a la población local.

EJE RECTOR 2	BIENESTAR SOCIAL					
Objetivo 2.4.	RESUMEN NARRATIVO	INDICADORES	MÉTODO DE CÁLCULO	MEDIOS DE VERIFICACIÓN	FRECUENCIA	SUPUESTOS
FIN	Promover un desarrollo urbano armónico	Cobertura de las obras de infraestructura y desarrollo urbano	(Habitantes beneficiados por las obras y el equipamiento urbano / Total de habitantes del municipio) * 100	Reporte de cobertura del servicio generado y ubicado en la Dirección de Obras Públicas	Semestral	Se cuenta con el programa de obra pública del municipio.
PROPÓSITO	El municipio crece de manera ordenada y sustentable	Cobertura de las obras de infraestructura y desarrollo urbano	(Habitantes beneficiados por las obras y el equipamiento urbano / Total de habitantes del municipio) * 101	Reporte de cobertura del servicio generado y ubicado en la Dirección de Obras Públicas	Semestral	Se cuenta con el programa de obra pública del municipio.
COMPONENTE 1	Regularizar la situación jurídica de los propietarios de inmuebles	Entregar 60% de títulos de propiedad solicitados	(Títulos de propiedad entregados / solicitudes de regularización) * 100	Sindicatura	Anual	La población que reclama inmuebles en situación de irregularidad cuenten con instrumentos para comprobar su posesión.
ACTIVIDAD 1	Gestiónar la regularización de la propiedad inmobiliaria	Oficio y acuse de recibido.	Contar con oficio y acuse de recibido	Oficio y acuse de recibido	Semestral	La población que reclama inmuebles en situación de irregularidad cuenten con instrumentos para comprobar su posesión.

EJE RECTOR 3	LA IGUALDAD EFECTIVA DE LOS DERECHOS Y EL ACCESO A SERVICIOS PÚBLICOS DE CALIDAD PARA TODAS Y TODOS					
Objetivo 3.1	RESUMEN NARRATIVO	INDICADORES	MÉTODO DE CÁLCULO	MEDIOS DE VERIFICACIÓN	FRECUENCIA	SUPUESTOS
FIN	Contribuir a mejorar la calidad de vida de los habitantes del Municipio mediante una amplia cobertura en la prestación de los servicios públicos de recolección de basura, limpieza, panteones, rastro, alumbrado público, telecomunicaciones, parques y jardines.	Cobertura del servicio de recolección de basura	(Viviendas particulares habitadas, que reciben el servicio de recolección de basura/ Total de viviendas particulares habitadas del municipio) * 100	Reporte de cobertura del servicio de recolección de basura 2020 generado y ubicado en la Dirección de Servicios Públicos Censo INEGI disponible en: https://www.inegi.org.mx/	ANUAL	Se cuenta con el Programa de Desarrollo Urbano actualizado. Se cuenta con el inventario de viviendas particulares del municipio.
		Cobertura del servicio de limpia	(mts lineales de tramos de calles y/o m2 de espacios públicos con servicio continuo de limpia/ Total de mts lineales de tramos de calles y/o m2 de espacios públicos del municipio) * 100	Reporte de cobertura del servicio de limpia 2020 generado y ubicado en la Dirección de Servicios Públicos Censo INEGI disponible en: https://www.inegi.org.mx/	ANUAL	Se cuenta con el Programa de Desarrollo Urbano actualizado. Se cuenta con el inventario de calles y espacios públclios del municipio.
		Cobertura del servicio de panteones	(Número de espacios disponibles para el depósito de restos humanos registrados por el municipio/ Demanda potencial de espacios para el depósito de restos humanos del muncipio) * 100	Reporte de cobertura del servicio de panteones 2020 generado y ubicado en la Dirección de Servicios Públicos. Censo INEGI disponible en: https://www.inegi.org.mx/	ANUAL	Existen panteones con espacios disponibles. Se cuenta con el inventario de espacios disponibles para el depósito de restos humanos en el municipio.
		Cobertura del servicio de parques y jardines	(m2 de superficie atendida / m2 de superficie total de parques y jardines del municipio) * 100	Reporte de cobertura del servicio de parque sy jardines 2020 generado y ubicado en la Dirección de Servicios Públicos Censo INEGI disponible en: https://www.inegi.org.mx/	ANUAL	Se cuenta con la participación de la sociedad. Se cuenta con el Programa de Desarrollo Urbano actualizado.
		Cobertura del servicio de Alumbrado Público	(mts lineales de tramos de calles y/o m2 de espacios públicos que disponen del servicio de Alumbrado Público con luminarias en buenas condiciones/ mts lineales totales de tramos de calles y/o m2 de espacios públicos del municipio)*100	Censo 2020 coordinado con Comisión Federal de Electricidad genrado y bicado en la Dirección de Servicios Públicos	ANUAL	Se cuenta con el Programa de Desarrollo Urbano actualizado. Se cuenta con el inventario de tramos de calles y espacios públicos del municipio
PROPÓSITO	La población del municipio, cuentan con una prestación de los servicios públicos de recolección de basura, limpieza, panteones, rastro, alumbrado público, parques y jardínes de calidad	Tasa de variación de denuncias y/o quejas ciudadanas de la prestación de los servicios públicos de recolección de basura, limpieza, panteones, rastro, alumbrado público, parques y jardínes.	[(Total de denuncias y/o quejas del año 2020 / Total de denuncias y/o quejas del 2019) -1] * 100 =%	Archivos de denuncias, quejas y sugerencias de la dependencia en el año 2020 Calculadora de seleccion de muestras por municipio proporcionado por INAFED disponible en: https://www.gob.mx/inafed	ANUAL	Disponibilidad de la ciudadanía para contestar la encuesta Situaciones climatologicas favorables.
COMPONENTE 1	Servicio de recolección de basura otorgado	Porcentaje de Residuos Sólidos Urbanos (RSU) recolectados y dispuestos adecuadamente.	(Volumen (Ton) de R.S.U. recolectados y dispuestos adecuadamente / Volumen total (Ton) de R.S.U. programados a recolectar y disponer adecuadamente) * 100	Reporte de rutas atendidas 2020 generadas y ubicadas en la Dirección de Servicios Públicos. Censo de viviendas del INEGI disponible en: https://www.inegi.org.mx/	SEMESTRAL	Situaciones climatologicas favorables Se cuenta con la infraestructura y equipo suficiente.
ACTIVIDADES 1.1	Reparación y mantenimiento de las unidades recoletoras existentes	Porcentaje de unidades en buen estado para recolectar la basura	(Número de unidades disponibles para prestar el servicio/Total de unidades con las que se cuenta para prestar el servicio)*100	Bitácora de mantenimiento y reparación de unidades de recolección de basura generada y ubicada en la Dirección de Servicios Públicos.	TRIMESTRAL	Se realiza buen uso de las unidades recolectoras de basura disminuyendo el mantenimiento correctivo.
ACTIVIDADES 1.2	Reparación y mantenimiento de contenedores de basura	Porcentaje de contenedores en buen estado	(Número de contenedores de basura disponibles /Total de contenedores de basura para prestar el servicio)*100	Bitácora de mantenimiento y reparación de conrtenedores de basura, inventario de contenedores generada y ubicada enr la Dirección de Servicios Públicos.	TRIMESTRAL	Se realiza un uso adecuado de contenedores de basura y eso logra aumentar su vida útil
ACTIVIDADES 1.3	Crear un programa de reciclaje y separación de basura	Porcentaje de basura reciclada	((peso de basura reciclada/total de la basura generada) * 100	Bitácora de reporte de actividades de la Dirección de Servicios públicos.		
COMPONENTE 2	Servicio de limpia otorgado y Rastro Municipal	Porcentaje de cumplimiento del programa de barrido	(Mts lineales barridos / Mts lineales programados) *100	Bitácora de Reportes de actividades de la Dirección de Servicios Públicos generado y ubicado en la Dirección de Servicios Públicos.	SEMESTRAL	Clima favorable Se cuenta con la infraestructura y equipo suficiente
ACTIVIDADES 2.1	Realización de una campaña de limpieza por elementos del personal de la direccion Municipal de Servicios públicos	Porcentaje de metas cumplidas	(Número de metas cumplidas/Total de metas programadas)*100	Reporte de metas cumplidas por la direccion municipal de servicios públicos y evidencia fotografica generada.	TRIMESTRAL	Se cuenta con la participación de la ciudadanía en las campañas de limpieza en calles, callejones, camellones y boulevares
ACTIVIDADES 2.2	Limpieza y/o mantenimiento del basurón Público Municipal	Porcentaje de mantenimiento	(Número de acciones de Mantenimiento realizadas/ Número de Acciones de mantenimiento programadas) *100	Reporte de metas cumplidas por la direccion municipal de servicios públicos y evidencia fotografica generada.	TRIMESTRAL	La dirección de Servicios Públicos realiza los mantenimientos necesarios en los espacios del basuron municipal
ACTIVIDADES 2.3	Servicio del Rastro Municipal	Porcentaje de servicios por sacrificio de cabezas de ganado o porcícolas	(Número de sacrificios realizados/ Número de sacrificios solicitados) * 100	Reporte de metas cumplidas por la direccion municipal de servicios públicos y evidencia fotografica generada.	TRIMESTRAL	Se solicitan los servicios del rastro municipal para el sacrificio de cabezas de ganado o porcícolas
COMPONENTE 3	Servicio de panteones municipales otorgado	Porcentaje de atención a la demanda del servicio	(Solicitudes atendidas para depósito o cremación de restos humanos/Total de solicitudes recibidas para depósito o cremación de restos humanos)*100	Reportes de atención a la demanda ciudadana del servicio de panteones generado y ubicado en la Dirección de Servicios Públclios Municipales	SEMESTRAL	Se cuenta con espacios disponibles para el depósito de restos humanos y hornos para incinerar cadáveres o restos humanos.
ACTIVIDADES 3.1	Mantenimiento y conservación de los panteones municipales	Porcentaje de cumplimiento al programa de mantenimiento y conservación de panteones	(Mts2 de espacios de panteón que recibieron algún tipo mantenimiento/Mts2 de espacios de panteón programados para mantenimiento)*100	Reportes de actividades de mantenimiento generado y ubicado en la Dirección de Servicios Públicos.	TRIMESTRAL	Se cuenta con la infraestructura y equipo suficiente Se cuente con un programa de mantenimiento y conservación de panteones municipales.
COMPONENTE 4	Parques y Jardines limpios	Porcentaje de atención a la demanda de limpieza y mantenimiento de parques y jardines	(M2 de parques y jardínes que recibieron limpieza y mantenimiento / M2 de área verdes que requieren limpieza y mantenimiento) * 100	Reportes de actividades en parques y jardines generado y ubicado en la Dirección de Servicios Públicos.	SEMESTRAL	Se cuenta con la infraestructura y equipo suficiente. Se cuenta con el inventario de áreas verdes o diagnóstico actualizado. Se cuenta con el Programa de Desarrollo Urbano con información disponible.
ACTIVIDADES 4.1	Forestación y reforestarciónáreas verdes	Porcentaje de cumplimiento del programa de forestación y reforestación de áreas verdes	(Árboles plantados en áreas verdes / Total de árboles programados ára plantear en áreas verdes) * 100.	Reportes de actividades en parques y jardines generado y ubicado en la Dirección de Servicios Públicos.	TRIMESTRAL	Se cuenta con la infraestructura y equipo suficiente Se cuente con un programa de forestación y reforestación Se cuenta con el inventario de áreas verdes o diagnóstico actualizado. Se cuenta con el Programa de Desarrollo Urbano con información disponible
ACTIVIDADES 4.2	Mantenimiento y Conservación de Estadios deportivos del Municipio	Porcentaje de Mantenimiento de Estadios deportivos del Municipio	(Total de Mantenimientos a estadios Deportivos realizados / Total de Mantenimientos a estadios programados) *100	Reportes de actividades en parques y jardines generado y ubicado en la Dirección de Servicios Públicos.	TRIMESTRAL	Se cuenta con la infraestructura y equipo suficiente Se cuenta con el inventario de estadios deportivos Se cuenta con el Programa de Desarrollo Urbano con información disponible
ACTIVIDADES 4.3	Mantenimiento y Conservación de Plazas y Canchas Públicas	Porcentaje de mantenimiento y Conservación de Plazas y Canchas Públicas	(Total de mantenimientos a plazas y canchas públicas realizadas/Total de mantenimientos a plazas y canchas públicas programados) *100	Reportes de actividades en parques y jardines generado y ubicado en la Dirección de Servicios Públicos.	TRIMESTRAL	Se cuenta con la infraestructura y equipo suficiente. Se cuenta con el inventario de áreas verdes o diagnóstico actualizado. Se cuenta con el Programa de Desarrollo Urbano con información disponible.
COMPONENTE 5	Servicio de Alumbrado Público otorgado	Porcentaje de atención de solicitudes de mantenimiento a la red de alumbrado público	(Número de solicitudes con respuesta positiva / Total de solicitudes recibidas)*100	Reportes de actividades de alumbrado público generado y ubicado en la Dirección de Servicios Públicos.	TRIMESTRAL	Se cuenta con la infraestructura y equipo suficiente
ACTIVIDADES 5.1	Mantenimiento y conservación de la red de Alumbrado Público	Porcentaje de la red de Alumbrado público con mantenimiento preventivo y correctivo	(Longitud (km) de la red con mantenimiento / Longitud total de la red (km))*100	Reportes de actividades de alumbrado público generado y ubicado en la Dirección de Servicios Públicos.	TRIMESTRAL	Se cuenta con la infraestructura y equipo suficiente
COMPONENTE 6	Garantizar la conectividad a internet en espacios públicos	Evidenciar servicio de internet en los espacios públicos seleccionados	Registro en trabajo de campo	Trabajo de campo	TRIMESTRAL	Se cuenta con la infraestructura y equipo suficiente
ACTIVIDADES 6.1	Gestionar la instalación de antena para servicio de internet por parte de la CFE	Oficio de solicitud de instalación de antena	Contar con oficio y acuse de recibido	Oficio y acuse de recibido	SEMESTRAL HASTA CONTAR CON LA OBRA	Existe disposición de la CFE por instalar la antena para el servicio de internet.

EJE RECTOR 3	LA IGUALDAD EFECTIVA DE LOS DERECHOS Y EL ACCESO A SERVICIOS PÚBLICOS DE CALIDAD PARA TODAS Y TODOS					
Objetivo 3.2	RESUMEN NARRATIVO	INDICADORES	MÉTODO DE CÁLCULO	MEDIOS DE VERIFICACIÓN	FRECUENCIA	SUPUESTOS
FIN	Garantizar el acceso oportuno a los servicios integrales de salud	Tasa de crecimiento de diagnósticos realizados	((Diagnósticos realizados en el año evaluado - Diaganósticos realizados en el año previo al evaluado) / Diagnósticos realizados en el año previo al evaluado) * 100	Registros del Centro de Salud Rural	Anual	El Centro de Salud proporciona el número de diagnósticos realizados.
PROPÓSITO	Los pobladores cuentan con acceso oportuno y de calidad a los servicios de salud	Tasa de crecimiento de diagnósticos realizados	((Diagnósticos realizados en el año evaluado - Diaganósticos realizados en el año previo al evaluado) / Diagnósticos realizados en el año previo al evaluado) * 100	Registros del Centro de Salud Rural	Semestral	El Centro de Salud proporciona el número de diagnósticos realizados.
COMPONENTE 1	Promover la prevención y atención oportuna de salud a la población del municipio	Número de programas de prevención y atención médicas	Cantidad de programas de prevención y atención médicas	Registro de los eventos, convocatorias, listas de asistencia	Semestral	Que existe interés de la población por la salud.
ACTIVIDADES 1.1	Gestionar los servicios de hospitalización para la región	Oficio y acuse de recibido por parte la Secretaría de Salud del Estado de Sonora	Contar con el oficio y acuse de recibido por parte la Secretaría de Salud del Estado de Sonora	Oficio y acuse de recibido por parte la Secretaría de Salud del Estado de Sonora	Anual	Que el Gobierno del Estado de Sonora cumpla con el compromiso expuesto en el Plan Estatal de Desarrollo
ACTIVIDADES 1.2	Contar con un servicio de ambulancia digno	Ambulancia digna	Contar con un vehículo de ambulancia con una edad no mayor a 10 años	Centro de Salud Rural	Anual	Que la ambulancia reciba el trato adecuado aún con una antigûedad no mayor a 10 años
ACTIVIDADES 1.3	Brindar apoyo de viáticos a la población con familiares en hospitales	Porcentaje de viáticos otorgados	(viáticos otorgados / viáticos solicitados) * 100	Solicitudes al ayuntamiento por motivo de viáticos causado por viaje a hospital	Trimestral	Que exista disponibilidad de recursos en el ayuntamiento.
ACTIVIDADES 1.4	Brindar brigadas de salud para los habitantes del municipio	Número de brigadas hechas	Número de brigadas hechas	Registro de brigadas llevadas a cabo	Anual	Que exista demanda de la población por las brigadas de salud
ACTIVIDADES 1.5	Campañas de esterilización de mascotas	Campañas de esterilización de mascotas y animales callejeros	Número de animales esterilizados	Registro de la campaña de esterilización	Anual	Que exista interés por parte de los pobladores para esterilizar a sus mascotas

EJE RECTOR 3	LA IGUALDAD EFECTIVA DE LOS DERECHOS Y EL ACCESO A SERVICIOS PÚBLICOS DE CALIDAD PARA TODAS Y TODOS					
Objetivo 3.3	RESUMEN NARRATIVO	INDICADORES	MÉTODO DE CÁLCULO	MEDIOS DE VERIFICACIÓN	FRECUENCIA	SUPUESTOS
FIN	Contribuir al Desarrollo Urbano del municipio, mediante la ejecución de obras de infraestructura y de equipamiento urbano	Cobertura de las obras de Infraestructura y Equipamiento Urbano	(Habitantes beneficiados por las obras y el Equipamiento Urbano / Total de habitantes del Municipio) x 100	Reporte de cobertura del servicio anualgenerado y ubicado en la Dirección de Obras Públicas. Censo de INEGI disponible en: https://www.inegi.org.mx/	ANUAL	Se cuenta con el Programa de Desarrollo Urbano actualizado. Se cuenta con el programa de obra pública del Municipio
PROPÓSITO	El municipio cuenta con obras de infraestructura y equipamiento urbano	Porcentaje de obras realizadas	(Total de obras concluidas / Total de obras que se iniciaron)*100	Reporte de cobertura del servicio anual generado y ubicado en la Dirección de Obras Públicas.	ANUAL	Se cuenta con el Programa de Desarrollo Urbano actualizado. Se cuenta con el programa de obra pública del Municipio
COMPONENTE 1	Vialidades del municipio son modernizadas y rehabilitadas	Porcentaje de modernización y rehabilitación de vialidades	(Superficie (m2) de vialidades pavimentadas o rehabilitadas / Superficie total (m2) de vialidades del Municipio)*100	Reporte de cobertuta del servicio por la Dirección de Obras Públicas, Programa Operativo Anual Reporte de metas de la Cuenta Pública, Reporte trimestral de avance financiero generados y ubicados en la Dirección de Obras Públicas	SEMESTRAL	Se cuenta con el Programa de Desarrollo Urbano actualizado. Se cuenta con el programa de obra pública del Municipio
ACTIVIDADES 1.1	Pavimentación de calles	Porcentaje de de pavimentación de calles	(Superficie (m2) de pavimento nuevo en calles / Superficie (m2) de pavimentos e	Reporte de cobertuta del servicio por la Dirección de Obras Públicas, Programa Operativo Anual Reporte de metas de la Cuenta Pública, Reporte trimestral de avance financiero generados y ubicados en la Dirección de Obras Públicas	TRIMESTRAL	Se cuenta con el Programa de Desarrollo Urbano actualizado. Se cuenta con el programa de obra pública del Municipio
ACTIVIDADES 1.2	Rehabilitación de calles con recarpeteo	Porcentaje de recarpeteo en la rehabilitación de calles	(Superficie (m2) de pavimentos en calles rehabilitados con recarpeteo / Superficie (m2) de pavimento en calles programadas para recerpeteo)*100	Reporte de cobertuta del servicio por la Dirección de Obras Públicas, Programa Operativo Anual Reporte de metas de la Cuenta Pública, Reporte trimestral de avance financiero generados y ubicados en la Dirección de Obras Públicas	TRIMESTRAL	Se cuenta con el Programa de Desarrollo Urbano actualizado. Se cuenta con el programa de obra pública del Municipio
ACTIVIDADES 1.3	Rehabilitación de calles con bacheo	Porcentaje de bacheo en las calles	(Superficie (m2) de bacheo ejecutado en las calles / Superficie (m2) de bacheo programado en las calles)*100	Reporte de cobertuta del servicio por la Dirección de Obras Públicas, Programa Operativo Anual Reporte de metas de la Cuenta Pública, Reporte trimestral de avance financiero generados y ubicados en la Dirección de Obras Públicas	TRIMESTRAL	Se cuenta con el Programa de Desarrollo Urbano actualizado. Se cuenta con el programa de obra pública del Municipio
ACTIVIDADES 1.4	Rehabilitación de caminos rurales	Metros o kilómetros de caminos rehabilitados	Metros o kilómetros de caminos rehabilitados	Reporte de cobertuta del servicio por la Dirección de Obras Públicas, Programa Operativo Anual Reporte de metas de la Cuenta Pública, Reporte trimestral de avance financiero generados y ubicados en la Dirección de Obras Públicas	TRIMESTRAL	Se cuenta con el programa de obra pública del municipio.
COMPONENTE 2	Obras de equipamiento urbano realizadas	Variación porcentual anual de la poblacion beneficiada con obras de infraestructura	(Habitantes beneficiados por las obras año actual / Habitantes beneficiados por las obras año anterior) *100	Reporte de cobertuta del servicio por la Dirección de Obras Públicas, Programa Operativo Anual Reporte de metas de la Cuenta Pública, Reporte trimestral de avance financiero generados y ubicados en la Dirección de Obras Públicas	SEMESTRAL	Se cuenta con el Programa de Desarrollo Urbano actualizado. Se cuenta con el programa de obra pública del Municipio
ACTIVIDADES 2.1	Mantenimiento, construcción y conservación de espacios públicos	Porcentaje de cumplimiento al programa de mantenimeinto, construcción y conservación de edificios, lugares y espacios públicos	(Espacios públicos rehabilitados, construido y/o con mantenimiento/ Espacios públicos programados a rehabilitar, construir y/o dar mantenimiento)*100	Reporte de cobertuta del servicio por la Dirección de Obras Públicas, Programa Operativo Anual Reporte de metas de la Cuenta Pública, Reporte trimestral de avance financiero generados y ubicados en la Dirección de Obras Públicas	TRIMESTRAL	Se cuenta con el Programa de Desarrollo Urbano actualizado. Se cuenta con el programa de obra pública del Municipio Contar con un inventario de espacios públicos que requieren algún tipo de mantenimiento, ampliación o conservación
ACTIVIDADES 2.2	Construcción de guarniciones en calles y avenidas y señalización instalada	Porcentaje de guarniciones construidas	(M2 de guarniciones construidas/M2 de calles y avenidas que requieren guarniciones)*100	Reporte de cobertuta del servicio por la Dirección de Obras Públicas, Programa Operativo Anual Reporte de metas de la Cuenta Pública, Reporte trimestral de avance financiero generados y ubicados en la Dirección de Obras Públicas	TRIMESTRAL	Se cuenta con el Programa de Desarrollo Urbano actualizado. Se cuenta con el programa de obra pública del Municipio Contar con un inventario de espacios públicos que requieren algún tipo de mantenimiento, ampliación o conservación.
ACTIVIDADES 2.3	Reparación, mantenimiento y adquisición de maquinaria para obras públicas	Porcentaje de maquinaria en buen estado	(Maquinaria disponible para obras públicas /Total de Maquinaria disponible para prestar el servicio)*100	Reporte de cobertuta del servicio por la Dirección de Obras Públicas, Programa Operativo Anual Reporte de metas de la Cuenta Pública, Reporte trimestral de avance financiero generados y ubicados en la Dirección de Obras Públicas	TRIMESTRAL	Se cuenta con el Programa de Desarrollo Urbano actualizado. Se cuenta con el programa de obra pública del Municipio
COMPONENTE 3	Rehabilitación y ampliación de la red de drenaje y saneamiento.	Porcentaje de rehabilitación y ampliación de la red de drenaje y saneamiento	(Superficie (m2) de drenaje ampliado o rehabilitadas / Superficie total (m2) de la red de drenaje del Municipio)*100	Reporte de cobertuta del servicio por la Dirección de Obras Públicas, Programa Operativo Anual Reporte de metas de la Cuenta Pública, Reporte trimestral de avance financiero generados y ubicados en la Dirección de Obras Públicas	SEMESTRAL	Se cuenta con el Programa de Desarrollo Urbano actualizado. Se cuenta con el programa de obra pública del Municipio
ACTIVIDADES 3.1	Elaborar un diagnóstico para identificar los espacios sujetos a rehabilitación y ampliación de la red de drenaje	Diagnóstico	Diagnóstico	Reporte de cobertuta del servicio por la Dirección de Obras Públicas, Programa Operativo Anual Reporte de metas de la Cuenta Pública, Reporte trimestral de avance financiero generados y ubicados en la Dirección de Obras Públicas	SEMESTRAL	Se cuenta con el Programa de Desarrollo Urbano actualizado. Se cuenta con el programa de obra pública del Municipio
ACTIVIDADES 3.2.	Gestionar recursos estatales y federales para la rehabilitación o ampliación de la red de drenaje.	Oficio y acuse de recibido	Oficio y acuse de recibido	Reporte de cobertuta del servicio por la Dirección de Obras Públicas, Programa Operativo Anual Reporte de metas de la Cuenta Pública, Reporte trimestral de avance financiero generados y ubicados en la Dirección de Obras Públicas	SEMESTRAL	Se cuenta con el Programa de Desarrollo Urbano actualizado. Se cuenta con el programa de obra pública del Municipio
ACTIVIDADES 3.3	Rehabilitación de laguna de oxidación	Verificación de obra en campo y registro de obra según las NOMs pertinentes en la materia.	Trabajo de campo y registros de obra	Trabajo de campo y registros de obra	ANUAL	Se cuenta con el Programa de Desarrollo Urbano actualizado. Se cuenta con el programa de obra pública del Municipio

EJE RECTOR 3	LA IGUALDAD EFECTIVA DE LOS DERECHOS Y EL ACCESO A SERVICIOS PÚBLICOS DE CALIDAD PARA TODAS Y TODOS					
Objetivo 3.4	RESUMEN NARRATIVO	INDICADORES	MÉTODO DE CÁLCULO	MEDIOS DE VERIFICACIÓN	FRECUENCIA	SUPUESTOS
FIN	Garantizar la conectividad vial de la cabecera municipal todo el año	Porcentaje de días sin conectividad vial	(total de días del año sin conectividad vial / total de días del año) * 100	Registros y vitácoras	Semestral	Las temporadas de lluvia suelen variar en intensidad.
PROPÓSITO	Existe acceso vial al pueblo todo el año	Porcentaje de días sin conectividad vial	(total de días del año sin conectividad vial / total de días del año) * 100	Registros y vitácoras	Anual	Las temporadas de lluvia suelen variar en intensidad.
COMPONENTE 1	Materializar las obras previstas para garantizar la conectividad vial	Porcentaje de avance del proyecto y obra del puente vehicular	(total de inversión destinada/ total de inversión presupuestada)*100	Reporte de cobertuta del servicio por la Dirección de Obras Públicas, Programa Operativo Anual Reporte de metas de la Cuenta Pública, Reporte trimestral de avance financiero generados y ubicados en la Dirección de Obras Públicas	Semestral	No hay sobreprecio en lo presupuestado.
ACTIVIDADES 1.1	Gestionar recursos estatales y federales para la construcción de un puente vehicular que dé acceso a la cabecera municipal	Oficio y acuse de recibido	Oficio y acuse de recibido	Oficio y acuse de recibido	Trimestral	Existe disposición de autoridades estatales por construir la obra vial
ACTIVIDADES 1.2	Contar con un proyecto ejecutivo del puente vehicular	Proyecto ejecutivo	Proyecto ejecutivo	Dirección de Obras Públicas	Trimestral	
ACTIVIDADES 1.3	Mantener el vado actual en condiciones óptimas para el cruce vehicular	Mantenimiento anual	(Superficie (m2) de mantenimiento ejecutado en el vado/ Superficie (m2) de mantenimiento programado en el vado)*100	Reporte de cobertuta del servicio por la Dirección de Obras Públicas, Programa Operativo Anual Reporte de metas de la Cuenta Pública, Reporte trimestral de avance financiero generados y ubicados en la Dirección de Obras Públicas	Trimestral	Se cuenta con el Programa de Obra Pública

EJE RECTOR 4	DESARROLLO ECONÓMICO, SEGURIDAD Y SUSTENTABILIDAD					
Objetivo 4.1	RESUMEN NARRATIVO	INDICADORES	MÉTODO DE CÁLCULO	MEDIOS DE VERIFICACIÓN	FRECUENCIA	SUPUESTOS
FIN	Promover un desarrollo económico local de manera incluyente y sustentable	Tasa de crecimiento de licencias de uso de suelo no habitacionales	((licencias de uso de suelo no habitacionales emitidas en el año evaluado - licencias de uso de suelo no habitacionales emitidas en el año previo al evaluado) / licencias de uso de suelo no habitacionales emitidas en el año previo al evaluado) * 100	Registro del Ayuntamiento	Semestral	Exista población interesada en organizarse para conformar nuevas unidades económicas.
PROPÓSITO	Nuevas fuentes de empleo, diversificación de las actividades económicas	Tasa de crecimiento de empleo en actividad turística	((Turistas registrados en el año a evaluar - turistas registrados en el año previo al evaluado) / turistas registrados en el año previo al evaluado) * 100	Registros, listas de asistencia, reportes	Semestral	Exista población interesada en organizarse para conformar nuevas unidades económicas.
COMPONENTE 1	Aprovechar el potencial turístico del municipio	Tasa de crecimiento de empleo en actividad turística	((Turistas registrados en el año a evaluar - turistas registrados en el año previo al evaluado) / turistas registrados en el año previo al evaluado) * 100	Registros, listas de asistencia, reportes	Anual	Exista población interesada en organizarse para conformar nuevas unidades económicas.
ACTIVIDADES 1.1	Crear un inventario actualizado de recursos y atractivos turísticos	Inventario de recursos y atractivos turísticos	Existencia del inventario	Lista de asistencia, talleres y fotografías	Anual	Interés particular de las dependencias de gobierno al cumplimiento.
ACTIVIDADES 1.2	Crear un padrón de casas de huéspedes que reciban a la población turista	Porcentaje de casas de huéspedes avaladas por el municipio	(Número de casas de huéspedes autorizadas / Número de solicitudes para ser casa de huéspedes) * 100	Registros y autorizaciones	Trimestral	Interés de los pobladores por aprovechar potencial turístico
ACTIVIDADES 1.3	Organizar una nueva cámara de turismo incluyente	Oficio de convocatoria pública	Contar con oficio de convocatoria pública	Documento, difusión del documento en boletines, reuniones, minutas	Semestral	Exista población interesada en formar parte de la cámara de turismo.
ACTIVIDADES 1.4	Crear un módulo de atención turística	Turistas atendidos al año	Cantidad de turistas atendidos al año	Registros de sitios turísticos y registros de hoteles	Anual	No representa un aumento importante al erario.
ACTIVIDADES 1.5	Festival cultural/gastronómico	Festival cultural	Número de festivales culturales	Eventos culturales realizados	Anual	Que los habitantes muestren interés por los valores y actividades culturales

EJE RECTOR 4	DESARROLLO ECONÓMICO, SEGURIDAD Y SUSTENTABILIDAD					
Objetivo 4.2	RESUMEN NARRATIVO	INDICADORES	MÉTODO DE CÁLCULO	MEDIOS DE VERIFICACIÓN	FRECUENCIA	SUPUESTOS
FIN	Fortalecer el desarrollo agrícola, pecuario y minero del municipio	Tasa de variación en el volumen de producción agropecuaria	((Volumen de producción agropecuaria del año evaluado - volumen de producción agropecuaria del año previo al evaluado) / volumen de producción agropecuaria del año previo al evaluado) * 100	Registros de Desarrollo Rural, SAGARHPA	ANUAL	Existe interés de la población por mantener las actividades económicas mencionadas.
PROPÓSITO	Se incrementan la rentabilidad de las actividades primarias y su derrama económica en la población	Tasa de variación en el volumen de producción agropecuaria	((Volumen de producción agropecuaria del año evaluado - volumen de producción agropecuaria del año previo al evaluado) / volumen de producción agropecuaria del año previo al evaluado) * 100	Registros de Desarrollo Rural, SAGARHPA	SEMESTRAL	Existe interés de la población por mantener las actividades económicas mencionadas.
COMPONENTE 1	Estimular acciones orientadas al desarrollo económico	Porcentaje de unidades de producción apoyadas para mejorar su capacidad productiva	(Unidades apoyadas para mejorar su capacidad productiva / total de unidades de producción o total de unidades solicitantes de apoyo) * 100	Registros de Desarrollo Rural, SAGARHPA, registro de solicitudes	SEMESTRAL	Existe interés de la población por mantener las actividades económicas mencionadas.
ACTIVIDADES 1.1	Crear cadenas de valor con las empresas mineras de la región.	Registro de empresas locales trabajando en el sector minero	Cantidad de empresas locales trabajando en el sector minero	Registro Federal de Causantes, SAT	SEMESTRAL	Existe interés de la población por crear cadenas de valor relacionadas a la minería
ACTIVIDADES 1.2	Gestionar apoyos estatales, nacionales y privados que promuevan la diversificación de los productos agrícolas.	Oficio y acuse de recibo	Oficio y acuse de recibo	Oficio y acuse de recibo	TRIMESTRAL	Existe interés en la población por emprender un negocio relacionado con las actividades agropecuarias
ACTIVIDADES 1.3	Fomentar el emprendedurismo empresarial en jóvenes por medio de gestiones para apoyos federales, estatales y del sector privado	Oficio y acuse de recibo	Oficio y acuse de recibo	Oficio y acuse de recibo	TRIMESTRAL	Existe interés en los jóvenes por emprender un negocio relacionado con las actividades agropecuarias y mineras
ACTIVIDAD 1.4	Otorgar facilidades y capacitación a mujeres que busquen emprender un negocio	Registro de solicitudes y asistencia a capacitaciones	Número de registro de solicitudes de apoyo y asistencia a capacitaciones	Registro de solicitudes de apoyo y asistencia a capacitaciones	SEMESTRAL	Exista interés por parte de las mujeres para conformar su propio negocio.
ACTIVIDAD 1.5.1	Mantener la infraestructura para el desarrollo agropecuario	Porcentaje de cumplimiento al programa de mantenimeinto, construcción y conservación de la infraestructura de la unidad de riego	(Infraestructura rehabilitada, construida y/o con mantenimiento/ Infraestructura programada a rehabilitar, construir y/o dar mantenimiento)*100	Reporte de cobertuta del servicio 2022 Programa Operativo Anual 2022 Reporte de Metas de la Cuenta Pública Reporte trimestral de Avance Financiero 2022 Plano de cobertura 2022 gnerados y ubicados en la	TRIMESTRAL	Se cuenta con el Programa de Desarrollo Urbano actualizado. Se cuenta con el programa de obra pública del Municipio Contar con un inventario de espacios públicos que requieren algún tipo de
ACTIVIDAD 1.5.2	Mantener la infraestructura para el desarrollo agropecuario	Porcentaje de cumplimiento al programa de mantenimeinto, construcción y conservación de represos	(Infraestructura rehabilitada, construida y/o con mantenimiento/ Infraestructura programada a rehabilitar, construir y/o dar mantenimiento)*100	Reporte de cobertuta del servicio 2022 Programa Operativo Anual 2022 Reporte de Metas de la Cuenta Pública Reporte trimestral de Avance Financiero 2022 Plano de cobertura 2022 gnerados y ubicados en la Dirección de Obras Públicas	TRIMESTRAL	Se cuenta con el Programa de Desarrollo Urbano actualizado. Se cuenta con el programa de obra pública del Municipio Contar con un inventario de espacios públicos que requieren algún tipo de mantenimiento, ampliación o conservación
ACTIVIDAD 1.6	Apoyos para la agricultura de traspatio	Porcentaje de apoyos otorgados	(Apoyos otorgados para el desarrollo de agricultura de traspatio / apoyos solicitados para el desarrollo de agricultura de traspatio) * 100	Registro de solicitudes	TRIMESTRAL	Existe interés de la población
ACTIVIDAD 1.7	Promover la localización de agroindustria, así como actividades que añadan valor a los productos agrícolas y pecuarios de la región (dulces, salsas de chiltepín, carne seca, bacanora, etc.)	Exposiciones y reuniones enfocadas en otorgar valor agregado a los productos agrícolas y pecuarios regionales	Número de exposiciones y reuniones enfocadas en otorgar valor agregado a los productos agrícolas y pecuarios regionales	Registros, convocatorias, folletos, listas de asistencia y minutas	SEMESTRAL	Existe interés en la población por crear productos basados en la producción agrícola y pecuaria regional

EJE RECTOR 4	DESARROLLO ECONÓMICO, SEGURIDAD Y SUSTENTABILIDAD					
Objetivo 4.3	RESUMEN NARRATIVO	INDICADORES	MÉTODO DE CÁLCULO	MEDIOS DE VERIFICACIÓN	FRECUENCIA	SUPUESTOS
FIN	Garantizar el estado de derecho para la promoción de un desarrollo económico competitivo e incluyente	Cumplir al 80% con el programa de trabajo para segurdidad pública.	(Total de acitividades realizadas / Total de actividades programadas) * 100	Programa de trabajo de seguridad pública, cronograma de actividades, informe de resultados.	Semestral	Pueden existir factores externos que impidan la ejecución de actividades.
PROPÓSITO	Los habitantes de San Felipe de Jesús prosperan en un ambiente de paz e igualdad de derechos	Atender en 80% las demandas relacionadas a la seguridad pública de los habitantes del municipio	(Total de demandas atendidas / Total de demandas realizadas) * 100	Control de solicitudes en materia de atención a la seguridad pública. Estatus de atención y avances. Informes, minutas, acuerdos, solicitudes.	Semestral	La población reporta o denuncia faltas o ilícitos cometidos.
COMPONENTE 1	Contar con un cuerpo policiaco capaz y efectivo, al servicio de la ciudadanía					
ACTIVIDADES 1.1	Contar con una vigilancia más activa, con atención oportuna a los reportes ciudadanos	Reportes atendidos	(Total de demandas atendidas / Total de demandas realizadas) * 100	Control de solicitudes en materia de atención a la seguridad pública. Estatus de atención y avances. Informes, minutas, acuerdos, solicitudes.	Trimestral	La población reporta o denuncia faltas o ilícitos cometidos.
ACTIVIDADES 1.2	Realizar continuas capacitaciones a los cuerpos policiacos	Capacitaciones	Cumplir al 90% con el programa de capacitación al personal de seguridad pública sobre aplicación de reglamentos, uso de armas, primeros auxilios y manejo de personas agresivas. Total de personal programado para capacitación vs personal capacitado.	Programa de capacitación actualizado, estatus de personal capacitado, constancias de capacitación emitidas, listas de asistencia, expedientes de capacitación por empleado, informes, seguimiento de capacitación para medir impacto de la capacitación.	Semestral	Mantener evidencia de las actividades. Los registros deberán estar al alcance y fácilmente recuperables.
ACTIVIDADES 1.3	Contar con el equipo necesario para llevar a cabo las labores de seguridad y paz	Diagnóstico de necesidad de equipo	Documento	Resgistro de inventario	Semestral	Interés particular de las dependencias de gobierno al cumplimiento.

XIII. BIBLIOGRAFÍA

Asamblea General de las Naciones Unidas. (2019). *Programa de las Naciones Unidas para el Desarrollo (PNUD) en México.* https://www1.undp.org/content/undp/es/home/sustainable-development-goals.html

COESPO. (2015). *Indicadores demográficos y socioeconómicos*. http://www.coespo.sonora.gob.mx/

COESPO. (2020). *Indicadores demográficos y socioeconómicos*. http://www.coespo.sonora.gob.mx/

CONAGUA & Subdirección General Técnica. Gerencia de Calidad del Agua. (2020). *Diagnóstico de calidad del agua subterránea con base en Sólidos Disueltos Totales*. http://sina.conagua.gob.mx/sina/tema.php?tema=calidadAgua&n=regional#&ui-state=dialog

Gobierno de México. (2019). *Plan Nacional de Desarrollo 2019–2024*. https://framework-gb.cdn.gob.mx/landing/documentos/PND.pdf

Gobierno de México. (2021a). *Centro Nacional de Prevención de Desastres*. https://www.gob.mx/cenapred

Gobierno de México. (2021b). *Información del Sistema de Información y Gestión Educativa de la SEP*. https://siged.sep.gob.mx/SIGED/

Gobierno de México. (2021c). *Servicio Meteorológico Nacional*. https://smn.conagua.gob.mx/es/

Gobierno de Sonora. (2021). *Distritos de Desarrollo Rural de la SAGARHPA SONORA*. https://sagarhpa.sonora.gob.mx/

INAFED (Instituto Nacional para el Federalismo y el Desarrollo Municipal). (1986). *Enciclopedia de los Municipios y Delegaciones de México* (Centro Nacional de Estudios Municipales de la Secretaría de Gobernación ed.). Estado de Sonora. http://www.inafed.gob.mx/work/enciclopedia/EMM26sonora/index.html

INEGI. (2016). *Marco Censal Agropecuario*. https://www.inegi.org.mx/programas/amca/2016/

INEGI. (2019a). •*Censo nacional de gobiernos municipales y demarcaciones territoriales de la ciudad de México*. https://www.inegi.org.mx/programas/cngmd/2019/

INEGI. (2019b). *Censos económicos*. https://www.inegi.org.mx/rnm/index.php/catalog/547

INEGI. (2020a). *Censos de población y vivienda 1990, 1995, 2000, 2005, 2010, 2015, 2020*. https://www.inegi.org.mx/programas/ccpv/2020/default.html

INEGI. (2020b). *Marco Geoestadístico*. https://www.inegi.org.mx/temas/mg/

Organización de las Naciones Unidas. (2015). *La Agenda 2030 y los Objetivos de Desarrollo Sostenible: Una oportunidad para América Latina y el Caribe*. https://www.un.org/sustainabledevelopment/es/development-agenda/

World Commission on Environment and Development. (1987). *Informe Brundtland: Our Common Future*. Oxford University Press.